Oppdr.nr. 136042

RAPPORT

Oppdragsgiver: Norges miljø- og biovitenskapelige universitet

28.01.2020

VERDIVURDERING NMBU ÅS

Foto: NMBU digitalt bildearkiv (2019)

Oppdrag	:	NMBUs eiendommer på Ås
Bygningstype	:	Universitet
Oppdragsadresse	:	Mange adresser i Ås kommune, 1430 ÅS
Matrikkelnummer	:	42/1 m.fl. – 0214 Ås
Hjemmelshaver	:	Norges Miljø- og Biovitenskapelige Universitet

Mandat

Etter anmodning fra eier Norges Miljø og Biovitenskapelige Universitet (NMBU) v/Kristin Kreul har OPAK AS v/Øystein Dieseth, Thomas Rochstad-Johannesen og Christian Kleivene besiktiget ovennevnte eiendom for å utarbeide en verdivurdering.

Eiendommen er NMBU sitt campus på ÅS som består av ulike skole-, forsknings og landbruksbygg. Eiendommen består av flere g.nr/b.nr med et samlet areal på ca. 3 899 daa ifølge oversendt eiendomsoversikt.

Beskrivelse og begrensning av oppdraget fra oppdragsgiver
Statsbygg, på oppdrag fra regjeringen, skal vurdere konsekvensene av å innlemme Campus Ås i statens husleieordning. I den forbindelse er det ønskelig med en vurdering av eiendommens verdi. Verdien skal brukes som beregningsgrunnlag for innføring i Statsbyggs balanse og fastsettelse av husleien, kapitalelementet.

Campus Ås, med Ås gård, består (pr. 2018) av ca. 100 bygninger, på ca. 145 000 m^2, samt samlokaliseringsprosjektet som er under bygging (ikke inkludert i vurderingen). Viktige deler av dagens bygningsmasse er oppført rundt 1900 og 1950-1960. Campus rommer også et av landets største parkanlegg, som omgir en historisk bygningsmasse.

I tillegg har NMBU ca. 20 bygninger fordelt på litt over 11 000 m^2 på Norderås, Vollebekk, Slørstad og Kjerringjordet. NMBU har til sammen 27 festeforhold inne på campus.

Eiendommene som omfattes av oppdraget er gårds- og bruksnr. 27/4, 37/2, 38/1, 40/1, 41/1, 42/1, 42/8, 42/193, 42/194, 42/107, 43/3 og 74/113 i Ås kommune.

I møte den 16.09.19 ble ulike metoder for verdsetting drøftet, og det ble diskutert frem tre ulike alternativer. Eiendommene skal vurderes i to alternativ med følgende forutsetninger:

1) Verdien skal fastsettes på bakgrunn av eiendommens gjenanskaffelsesverdi, dvs. **teknisk verdi.**
2) Eiendommens markedsverdi, ved salg **uten statlig leiekontrakt** med tilsvarende bruk som i dag, men på **markedsmessige betingelser**. Eiendommen takseres iht. påregnelig utnyttelse (gjeldende regulering og kommuneplan).

Dokumenter/opplysninger

Følgende dokumenter er overlevert fra oppdragsgiver:

Fredede eiendommer i landsverneplan for Kunnskapsdepartementet
Campusplan 2019-2023-2040
Informasjonsskriv med oversikt over planer, eiendommer, festforhold
Bygningsoversikt
Driftsplan skogen
Tiltaksundersøkelse for gammelt avfallsdeponi Korsegårdsmyra
Eiendomsoversikt
Prosjektbeskrivelse for Tandbergkvartalet og innspill til områdereguleringsplan for Ås sentralområde
Avtale om oppdemming av Årungen

Vi har i tillegg innhentet følgende opplysninger:

Eiendomsinformasjon fra Nordeca Insight

Referanser

Befaringen:

Befaringsdato	: 16., 17., og 18. november 2019
Fra oppdragsgiver	: Ingen av oppdragsgivers representanter var med på befaringen. Vaktmester Eddy var delvis med en av dagene.
Fra Veridian	: Per Erik Solem
Fra OPAK	: Christian Kleivene og Thomas Rochstad-Johannesen
Ikke besiktiget	: Flere rom var i bruk til undervisning/forskning. Enkelte mindre rom ble ikke befart. Vi hadde også begrenset adkomst i fjøs og andre driftsbygninger.

Forutsetninger

Verdivurderingen er basert på følgende forutsetninger:

- Ikke kontrollert om det er miljøfarlige stoffer i grunn eller bygninger
- Forurensninger er selgers ansvar
- Ikke kontrollert om det er tinglyste servitutter eller ledningsnett i grunn
- Ikke kontrollert ferdigattest, om dagens bruk er tillatt og om det er offentlige påbud
- Ikke kontrollert fundamentering
- Ikke foretatt vedlikeholds- og tilstandsvurdering av bygg og tekniske anlegg
- Forutsatt fraflyttet og klar for ny utleie basert på markedsleie

Beliggenhet

Beliggenheten er vist på kart nedenfor, hvor eiendommen er markert

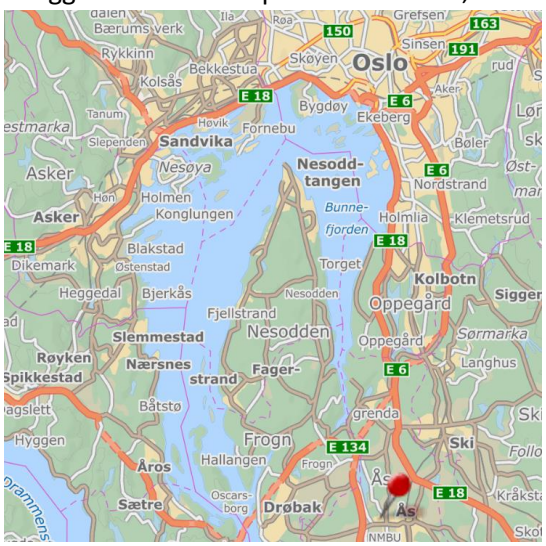

Den vurderte eiendommen er beliggende i Ås, som ifølge Ås kommune sine nettsider (2018) ligger ca. 3,5 mil sør for Oslo. Ås kommune er litt over 100 km^2 i utbredelse, preget av et åpent kulturlandskap som domineres av landbruksarealer. I Ås sentrum ligger det et rådhus med tilhørende kulturhus, jernbanestasjon som tilhører Østfoldbanen.

Ifølge SSB bor det 20 296 innbyggere i Ås kommune per 2. kvartal 2019. Forventet innbyggertall i 2030 er 27 088 og 34 029 innbyggere i 2040. Det vil si at ca. 700 nye innbyggere gjennomsnittlig årlig de neste 20 årene.

Det er kort vei til offentlig kommunikasjon som er busstoppene Vollebekk, Universitet i Ås og Åsgård skole som ligger på Drøbakveien sør for campus. Campusen ligger ca. 1,5 km vest for Ås stasjon. Både E18 og E6 går gjennom kommunen.

Planstatus

Kommuneplan

Planområde	: KPL_15-27
Tidsperiode	: 2015-2027
Ikrafttredelsesdato	: 03.02.2016
Formål for vurdert eiendom	: Offentlig eller privat tjenesteyting nåværende, friluftsområde nåværende, LNFR nåværende, næringsbebyggelse fremtidig, kombinert formål fremtidig og boligbebyggelse nåværende.
Båndleggingssone	: Deler av området (skravert) er båndlagt med hensynsonenavn H730_2 som ifølge planbestemmelsene gjelder forskrift om fredning av Statens kulturhistoriske eiendommer.
Gjennomføringssone	: Den østlige delen av planområdet er angitt med gjennomføringssone «fornyelse» H830_1 Sørhellinga. I planbestemmelsene fremgår det at fornyelsesområdet på Sørhellinga skal utbygging føre til høyere områdetetthet og større grad av flerfunksjonalitet.

Nedenfor er vist utsnitt av kommuneplankartet:

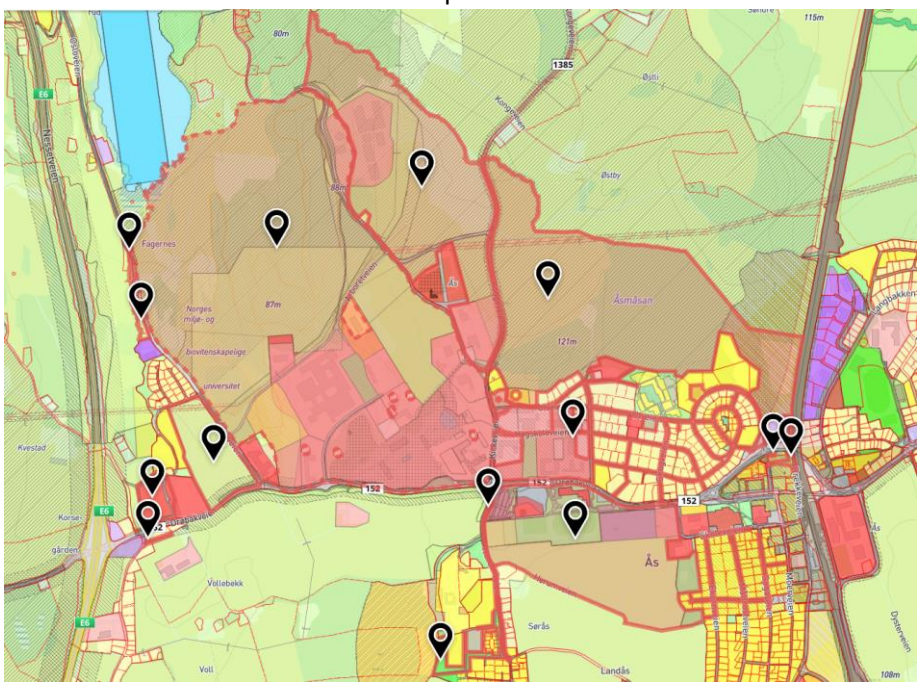

På kartet er g.nr/b.nr 42/1 markert

Sør/øst i området mot Ås sentrum er det avsatt et fremtidig næringsareal (N4) og offentlig eller privat tjenesteyting (O3). Nord i Ås sentrum er det et område som er avsatt til fremtidig kombinert bebyggelse. NMBU eier også en del av et kvartal i Ås sentrum som er tiltenkt utviklet til kombinert formål.

Reguleringsplan for Campus/NMBU Hovedbruk

Planområde	:	Campus ÅS
Ikrafttredelsesdato	:	20.06.2012
Formål for vurdert eiendom	:	Offentlig eller privat tjenesteyting, fjernvarmeanlegg, angitt bebyggelse og anleggsformål kombinert med angitte hovedformål, kjøreveg, fortau, torg, gang-/sykerlvei, gangveg/gangareal, annen veggrunn, kollektivholdeplass, parkering, grønnstruktur, park, angitt grønnstruktur kombinert med andre hovedformål, LNFR og landbruksformål.
Grad av utnytting	:	Ulik utnyttelse i de forskjellige feltene, mellom 15-100% BYA og ulike byggehøyde inntil 21 over planert terreng (et lite område vil kunne være 28 meter over terreng ved fallende terreng).
Rekkefølgebestemmelser	:	Rekkefølgekrav om rundkjøring, bussholdeplass, gang- og sykkelvei.

Nedenfor er vist utsnitt av reguleringskartet, hvor den vurderte eiendom er markert:

Reguleringsplan Damstykket – NLH (Campus Syd)

I sørøstlig hjørne på overnevnte plankart er et område som omtales i en oversikt vi har fått tilsendt som campus syd. I kommuneplanen er området avsatt som offentlig eller privat tjenesteyting og grøntareal. I ReguleringsplanID 032 som trådde i kraft 28.01.1980 er området regulert offentlige bygninger, park og jordbruk

Reguleringsplan for Einarstujordet (Ås gård)

Areal og bygg innenfor feltene kan benyttes til: Landbruksformål med husdyrrom, fôrlager, gjødsellager, verksteder, forskning, undervisning, administrasjon og fellesfunksjoner. Publikumsrettet virksomhet for de fagfelt som har sin virksomhet i området, herunder besøksgård. Parkeringsareal inngår ikke i BRA. Maksimal utnyttelsesgrad OP1: 31000 m2 BRA. Maksimal kotehøyde for møne = C + 97,0. Høydeforskjellen mellom møne og laveste ferdig planert terreng, skal ikke overskride 15 meter.

Ifølge Nordeca Insight er området bebygd med ca. 16 250 m^2 BRA.

Andre reguleringsplaner til de oppgitte matrikkelen
Vi har mottatt en oversikt over alle NMBU sine eiendommer. Vi har kort gjennomgått reguleringsstatuen til disse:

Kjerringjordet (43/3)
Kjerringjordet er uregulert men avsatt til offentlig eller privat tjenesteyting nåværende i Ås kommuneplan 2015-2017, som trådde i kraft 03.04.2013.

Tomten er bebygget.

Vollebekk (43/3)
Vollebekk er uregulert men avsatt til offentlig eller privat tjenesteyting nåværende i Ås kommuneplan 2015-2017 som trådde i kraft 03.04.2013.

Tomten er bebygget.

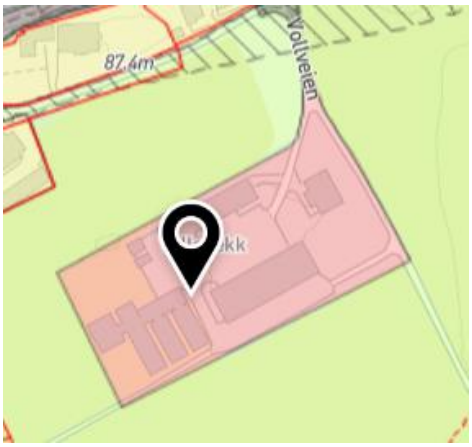

Korsegårdsmåsan (27/4)
Korsegårdsmåsan er uregulert, men avsatt til LNFR i Ås kommuneplan 2015-2017 som trådde i kraft 03.04.2013. Eiendommen er også angitt med hensynssone H570_3 «Bevaring av kulturmiljø».

Tomten er ubebygd og består av tettvokst skog.

Halå gård (37/2)
Halå gård er uregulert, men avsatt til LNFR i Ås kommuneplan 2015-2017 som trådde i kraft 03.04.2013. Eiendommen er også angitt med hensynssone H560_3 «Bevaring av naturmiljø»

Tomten er ubebygd og består av ca.:
60 % dyrket mark
40 % tettvokst skog og annen variert vegetasjon

Berg (38/1)
Berg er regulert til jordbruk og skogbruk (L1) i planID 033, som trådde i kraft 28.01.1980. I gjeldende kommuneplan er området avsatt til LNFR.

Tomten er ubebygd og består av ca.:
25 % dyrket mark
75 % tettvokst skog og annen variert vegetasjon.

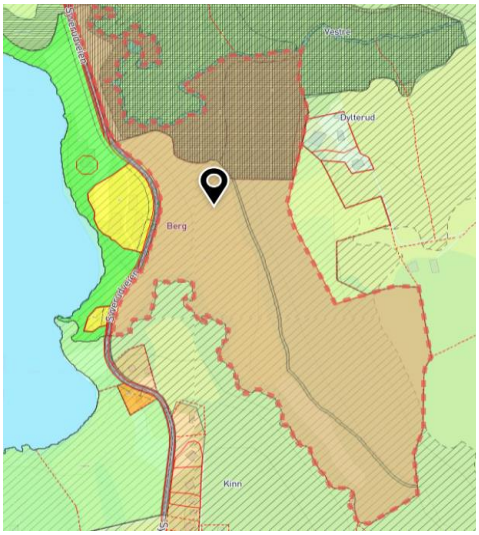

Kinn (40/1)
Kinn er uregulert men avsatt LNFR i Ås kommuneplan 2015-2017 som trådde i kraft 03.04.2013. Eiendommen er også angitt med hensynssone H560_3 «Bevaring av naturmiljø»

Tomten er ubebygd og består av ca.:
35 % dyrket mark
65 % tettvokst skog og annen variert vegetasjon.

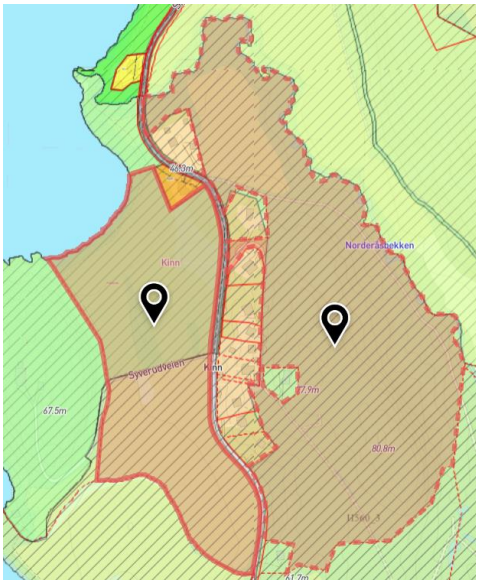

Norderås (41/1)
Norderås er uregulert, men avsatt til LNFR i Ås kommuneplan 2015-2017 som trådde i kraft 03.04.2013. Eiendommen er også delvis angitt med hensynssone H570_2 «Bevaring av kulturmiljø»

Tomten er bebygget og består av både dyrket mark og tettvokst skog fordelt ca.:
40 % dyrket mark
60 % tettvokst skog og variert vegetasjon

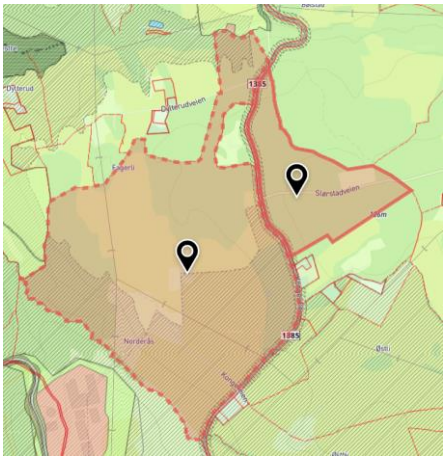

Brønnerud Skole (42/8)
Brønnerud skole er avsatt til offentlig eller privat tjenesteyting i Ås kommuneplan 2015-2017 som trådde i kraft 03.04.2013. Eiendommen er regulert til offentlig bebyggelse i reguleringsplanID 186 som trådde i kraft 28.04.1999.

Maks tillatt bebygd areal (BYA) er 20 %. Maks mønehøyde 11,5m og gesims 8,5.

Tomten er bebygget med flere bygg.

Høgskoleveien 16 (42/193)
Høgskoleveien 16 er bebygget med en enebolig og et uthus. Tomten har et areal på 1 367,8 m^2. Eiendommen omfattes av OP20 og er regulert til offentlig eller privat tjenesteyting i reguleringsplan for Campus Ås, vedtatt i kommunestyret 20.06.2012.

Tomten er festet bort til Ås Kommune.
Festeavgift er ikke oppgitt i mottatt oversikt over festeavtaler.

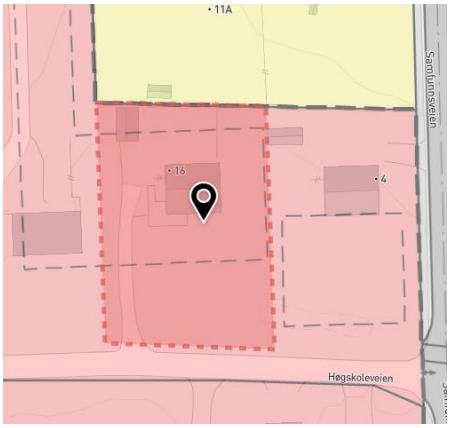

Samfunnsveien 4 (42/194)
Høgskoleveien 16 er bebygget med en enebolig og et uthus. Tomten har et areal på 1 186,6 m^2. Eiendommen omfattes av OP20 og er regulert til offentlig eller privat tjenesteyting i reguleringsplan for Campus Ås, vedtatt i kommunestyret 20.06.2012.

Kajaveien 18A (42/107)
Kajaveien 18 A er avsatt til boligbebyggelse i Ås kommuneplan 2015-2017 som trådde i kraft 03.04.2013. Eiendommen er regulert til frittliggende småhusbebyggelse (BV1) i reguleringsplanID 125 som trådde i kraft 22.11.1995. Maks tillatt bebygd areal (BYA) er 15% av tomtens nettoareal.

Tomten er festet bort. Årlig festeavgift er oppgitt til kr. 0

Bjørnebekkjordene (74/113)
Bjørnebekkjordene er uregulert men avsatt LNFR og fremtidig friområde (mørkere grønt areal i nordvestenden) i Ås kommuneplan 2015-2017 som trådde i kraft 03.04.2013.

Tomten består i hovedsak av dyrket mark

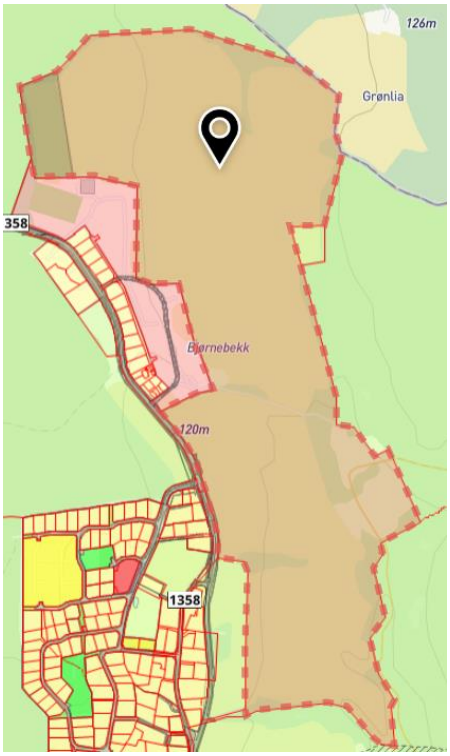

Tomtene

Ifølge oversendt oversikt over eiendommer på NMBU ÅS fremgår følgende tomteinformasjon:

Eiendomsnavn	G.nr/ b.nr	Eiet/ leid	Sum areal daa grunneiendom	Eiendomsinformasjon
Korsegårdsmåsan	27/4	Eid	56,9	Hjemmel til NMBU 8. januar 1918.
Hala gård	37/2	Eid	89	Hjemmel til NMBU 10. januar 1995.
Berg	38/1	Eid	186	Hjemmel til NMBU 19. januar 1984. Auksjonsskjøte
Kinn	40/1	Eid	163,7	Hjemmel til NMBU 29. januar 1970.
Norderås	41/1	Eid	827,7	Hjemmel til NMBU 19. mai 1949. Innovasjon Norge pantehaver i leiekontrakt
NMBU Hovedbruk	42/1	Eid	2881,9	Hjemmel til NMBU 25. juni 1964. Omfattende registrering i grunnboken
Brønnerud skole, Drøbakveien 63	42/8	Eid	18,3	Hjemmel 902599, festes av Ås kommune
Kajaveien 18A	42/107	Eid	1,44	Hjemmels havere 203486 25/6/1964 Registrert i grunnboken, SiÅs fester (99år)
Kjerringjordet og Vollebekk	43/3	Eid	460,9	Hjemmel til NMBU 31. juli 1899. Areal 30. oktober 2014 overført til 42/1.
Bjørnebekk	74/113	Eid	536,4	Hjemmel til NMBU 14. mai 1997. Forbud mot salg uten samtykke
Sum eid areal			**5 222**	

Tomtene er vist på kartet under:

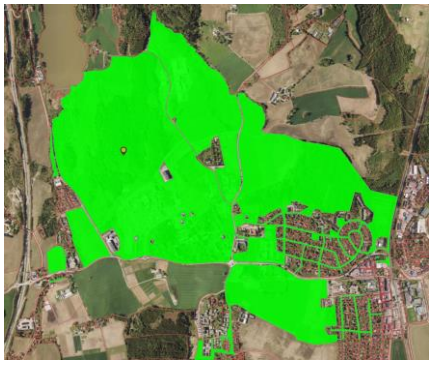

42/1 NMBU Hovedbruk

27/4 Korsegårdsmåsan

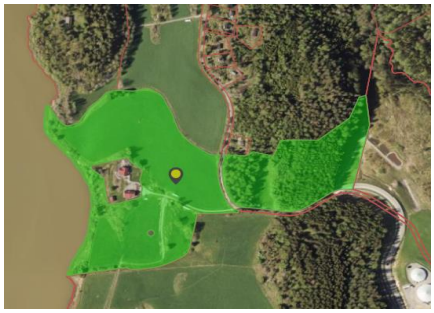

37/2 Hala Gård

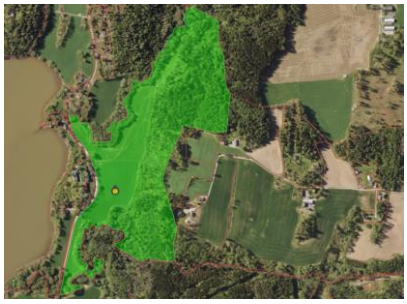

38/1 Berg

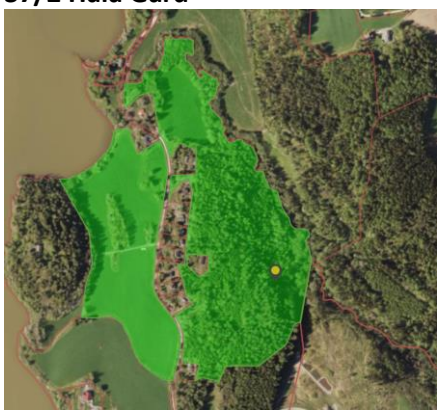

40/1 Kinn

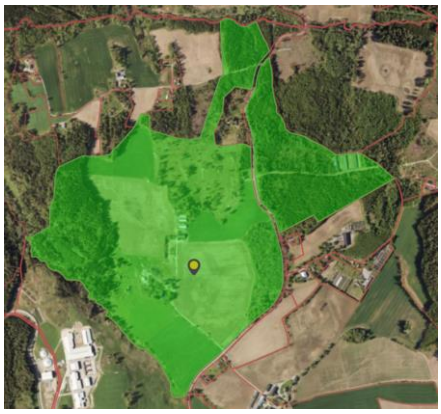

41/1 Norderås



42/8 Brønnerud skole

42/107 Kajaveien 18A

43/3 Kjerringjordet

74/113 Bjørnebekk

Store deler av tomtene er jordbruk eller skogområder.

Ifølge oversendt underlag er det oppgitt følgende festetomter:

Festeavtaler innenfor 42/1	G.nr/b.nr /f.nr	Sum grunn daa	Fester
Utveien 23, Kaja Barnehage	42/1/102	2,03	Kaja Barnehage
Høgskoleveien 26, friareal Kaja barneh.	42/1/274	2,53	Stiftelsen Kaja barnehage
Skogveien 22-28, SiÅs Stud bol.	42/1/245	16,50	Ny festeavtale - sammenslåing og tilføying er under utarbeidelse
Utveien 26,SiÅs	42/1/106	2,38	SiÅs
Utveien 29 SiÅs	42/1/105	2,15	SiÅs
Lyngskogen garasjer	42/1/221	3,32	Roar Moe. De vurderer å kjøpe, men har ikke henvendt seg skriftlig
Lyngveien 36	42/1/10	1,94	Finn Andersen
Høyskoleveien 11 og 13, Kajav. 16 og Samfunnsv 2	42/1/266	4,78	Studenskipnaden i Ås
Høyskolev. 6, 8, 10, Utveien 1, 3, 7 nibio	42/1/78	19,83	LMD, vil kjøpe. Festet av Norsk institutt for skogforskning
Høskoleveien 7, Kirkevei 3 og 5 NIBIO	42/1/99	0,80	LMD, vil kjøpe - er pkt. feste - Statens plantevern
Fougnerbakken 19, SiÅs	42/1/268	0,00	Pkt. feste - SiÅs
Utveien 2, Åkebakke barnehage	42/1/278	0,00	Privat
Herumveien 6, Treningssenter SiÅs	42/1/279	0,00	SiÅs
Pentagonveien 2, 4 SiÅs	42/1/193	6,71	SiÅs
Pentagon diverse SiÅs	42/1/196	24,95	SiÅs
Pentagon Parkering SiÅs	42/1/273	5,47	SiÅs
Skoleveien 14, Sørråsteigen B.hage, Ås kommune	42/1/220	7,32	Ås kommune
Arboretveien 8 og 10, Fortek	42/1/267	0,00	pkt feste. Senter for forteknologi AS. AS kjøpt av NMBU - ikke løst feste
SA Kaja Garasjer	42/1/88		Sagt opp festeavtale, leieavtale med kort oppsigelsestfrist er inngått
Lyngveien 2A	42/1/181		Kjøpt hus av Holm og Johannessen. Ny avtale. Sten Richard Larsen
Bregnevn 17	42/1/232		Bage Bråten Monsen
Måltrostvn 6A	42/1/255		Margaret Diana Westgård
Utveien 6	42/1/269		SiÅs
Kajaveien 15	42/1/133		SiÅs
Osloveien 1, Nofma	42/1/244	16,38	Selskapet for landbrukets næringsmiddelforskning
Mellombygget	42/1/263		Stiftelsen Fondet av jord- og myrundersøkelser
Sagabygget	42/1/265		Itas
Bregneveien 26	42/1/210		Arne Skjelvåg
Statskraft Varme	42/1/275		Statskraft Varme AS
Måltrostveien 6B	42/1/256		Berit og Per Lea
Bregneveien 22	42/1/208		Jon Fiskvik Otnes
Sum festet bort		**117,08**	

Kommentar til festeforholdene:
Det er i alt 35 festeforhold på matrikkel 42/1. OPAK har kun mottatt en oversikt over festeforholdene og ikke hver enkelt festekontrakt. Festeavgiften varierer, flere festeforhold er ikke oppgitt med areal og/eller årlig festeavgift og vi forutsetter her at disse festeforholdene som ikke er oppgitt med festeavgift ikke gir noen kontantstrøm.

Iht. mottatt oversikt har vi fått oppgitt en total årlig festeavgift på kr. 889 977 pr. år.

Verdien av festeforholdene
Vi har ikke mottatt festekontraktene og er ikke kjent med vilkår, lengde eller opplysninger om reguleringsbestemmelser. Festerenten ligger normalt i spennet 3 – 6 % avhengig av kontraktens innhold. Basert på de opplysningene vi har fått oppgitt har vi valgt en kapitaliseringsrente på 4,5 %. Eierkostnader vurderes til 5 % av brutto festeavgift.

Festeforholdene gir følgende verdi basert på våre innsatsfaktorer;
(Kr. 889 977 pr. år x 0,95) / 4,5 x 100 = kr. 18 788 409, som avrundes til kr. 18 800 000

Tomtens potensiale

Basert på gjeldende reguleringsplan kan Campusdelen av tomten g.nr/b.nr 42/1 bebygges med:

5.3 OP1, OP2, OP4 – OP22, utnyttelsesgrad og byggehøyder

Felt	Maks kotehøyde	Maks gesimshøyde ifht. gjennomsnittlig planert terreng	Forslag (i % BYA)
OPB1-OPB7	Alle eksisterende bygninger i sentralområdet som ikke er verneverdige. Ingen særskilte høydebestemmelser.		100 (Bygning dekker felt)
OP1	Parkering. Ingen bygningsmessige tiltak.	Parkering. Ingen bygningsmessige tiltak	Ingen
OP2	Maks mønehøyde: C = + 82,0 m	16, 0 m	60
OP4	Maks mønehøyde: C = + 80,0	17,0 m	50
OP5	Maks gesimshøyde: C = + 98,0 m innenfor byggegrense for østlige del av feltet. Maks gesimshøyde: C = + 88, 0 m innenfor byggegrense for vestlige del av feltet.	21,0 m innenfor byggegrense for østlig del av feltet. Ved fallende terreng vil et lite område kunne være 28 m over terreng 18, 0 m innenfor byggegrense for vestlig del av feltet.	60
OP6	Maks gesimshøyde: C = + 98,0 m	21,0 m	50
OP7	Maks gesimshøyde: C = + 90,0 m	13,0 m	40
OP8	Maks gesimshøyde: C = + 95,0 m	15, 0 m	50
OP9	Eksisterende høyder på bygninger beholdes.	Eksisterende høyder på bygninger beholdes	Eksisterende % BYA opprettholdes
OP10	Maks gesimshøyde: C = + 99,0 m	12,0 m	50
OP11	Maks gesimshøyde: C = + 103,0 m	12,0 m	100
OP12	Maks gesimshøyde mot Syverudveien C = +114,2 m Maks gesimshøyde mot Kongevn. C= +116,0	9,5 m mot Syverudveien 16,0 m mot Kongeveien	40
OP13	Maks gesimshøyde C=+112,0 m	8,5m	40

OP14	Maks gesimshøyde: C = +109,5	8,5 m	40
OP15	Maks mønehøyde 4 m fra gjennomsnittlig planert terreng	Maks mønehøyde 4 m fra gjennomsnittlig planert terreng	Maks 30 kvm BRA per bygning
OP16	Maks gesimshøyde: C = + 96,2 m Maks mønehøyde: C = +100,8 m	12,0 m	15
OP18	Maks mønehøyde: C = + 120,0 m	14,0 m	50
OP19	Maks mønehøyde: C = + 120,0 m	17,5 m	50
OP18	Maks mønehøyde: C = + 120,0 m	14,0 m	50
OP19	Maks mønehøyde: C = + 120,0 m	17,5 m	50
OP20	Maks mønehøyde: C = + 117,0 m	17,5 m	50
OP21	Maks gesimshøyde: C = 107,5 m	12,6 m	40
OP22	Eksisterende høyde på Damgården opprettholdes	Eksisterende høyde opprettholdes	Eksisterende % BYA opprettholdes
OP23	Maks mønehøyde inn mot torget: C = + 116,0 m Maks mønehøyde mot G1 og Samfunnsveien: C = + 113,0 m	Inn mot torget: 18,2 m Mot G1 og Samfunns-veien 13,5 m	60

Utregning av nytt potensiale

Felt	Feltareal	Foreslått BYA %	BYA kvm	Maks gesimshøyde m	Ca. tilsvarende ant etasjer	BTA
OPB1	2 600	100 %	2 600	12	4	10 400
OPB2	700	100 %	700	12	4	2 800
OP1	14 700	0 %	-	Ingen bygningsmessige tiltak		-
OP2	15 000	60 %	9 000	16	5	45 000
OP4	11 400	50 %	5 700	17	6	34 200
OP5	74 900	60 %	44 940	18-28	4	179 760
OP6	17 000	50 %	8 500	21	7	59 500
OP7	6 100	40 %	2 440	13	4	10 573
OP8	16 500	50 %	8 250	15	5	41 250
OP9	146 000	Eksisterende BYA% og høyde opprettholdes				-
OP10	5 000	50 %	2 500	12	4	10 000
OP11	1 000	100 %	1 000	12	4	4 000
OP12	33 000	40 %	13 200	9,5-16	4	52 800
OP13	15 900	40 %	6 360	8,5	3	18 020
OP14	14 100	40 %	5 640	8,5	3	15 980
OP15	15 800	Maks 30 kvm BRA per bygg		4	1	-
OP16	1 300	15 %	195	12	4	780
OP18	8 200	50 %	4 100	14	5	19 133
OP19	19 000	50 %	9 500	17,5	6	55 417
OP20	5 200	50 %	2 600	17,5	6	15 167
OP21	11 200	40 %	4 480	12,6	4	18 816
OP22	6 900	Eksisterende % BYA og høyde opprettholdes				-
OP23	33 700	60 %	20 220	13,5-18,2	4	80 880
SUM	**475 200**					**661 276**

Planområdet utgjør ca. 800 daa. av de totalt 2 881 daa som er oppgitt i eiendomsoversikten for g.nr/b.nr 42/1 NMBU hovedbruk. Feltene med utbyggingspotensiale utgjør ifølge reguleringsplan ca. 475 daa. Enkelte av områdene har ingen oppgitte begrensninger i byggehøyder, slik at vi har lagt

inn påregnelig utnyttelse iht. omkringliggende bebyggelse. Noen områder oppgis at eksisterende %BYA og høyde skal opprettholdes. Område OP5 som har et potensial på neste 180 000 m^2 BTA utvikles i dag til Veterinærhøyskole- og institutt. De nye veterinærbygningene blir ca. 63 000 m^2 BTA ifølge NMBU(2019).

Eksisterende bygningsmasse er oppgitt til ca. 150 000 m^2 BTA. Det vil si at det er et potensial på nesten 500 000 m^2 BTA på hele planområdet. Det er tilsynelatende et betydelig potensiale på eiendommen, som sannsynligvis vil ta flere år å utnytte.

<u>Utbyggingsplaner</u>

Campusplanen 2019-2023-2040

Ifølge Campusplanen ble gjeldende reguleringsplan for campus Ås vedtatt i 2012. Denne gir et avklart utbyggingspotensial for sentrale deler av campus, og er slik sett et godt redskap for videreutvikling av universitetsområdet. I tillegg arbeides det i disse dager med en områdeplan for Ås sentrum hvor det pekes på betydningen av å se utviklingen av campus Ås og tettstedet Ås i sammenheng.

På kort sikt fremgår det av arealregnskapet 2014-2023 at det skal utvikles 68 950 m^2 nye bygg i perioden. På samme tid skal det selges, rives, og avhendes 87 793 m^2 BTA bygg.

Arealregnskap 2014 - 2023	kvm
Revet	28 027
Kan/bør rives	6 628
Avhending (eid og leid)	53 138
Nye bygg	68 950
Resultat (arealreduksjon)	**18 843**
Prosentvis reduksjon	**9**

Det fremgår av campusplanen at gjeldende reguleringsplan legger opp til en utvikling av campus øst, nærmest mulig Ås tettsted og stasjon, for å underbygge utviklingen av universitetsbyen frem mot 2040. Fortettingspotensialet innebærer en dobling av eiendomsmassen fram mot 2040 i campus øst.

På lang sikt skal "*NMBU skape et nasjonalt og internasjonalt kraftsenter for forskning, utdanning og innovasjon innen sine fagområder*.» I tråd med helhetsplanen for campus Ås 2010–2100 som danner grunnlaget for nåværende regulering, legges det opp til å samle NMBUs aktiviteter langs en akse fra campus sør via campus øst, sentralcampus og til campus vest, med felles møteplasser inne og ute. Det fremgår at Campus øst har et stort potensiale for å bli et viktig område til næringsutvikling og nye kompetansemiljøer. Kommuneplanen 2015-2027 har avsatt delområdet campus øst med hensynssone for omforming og fornyelse. I henhold til kommuneplanen, skal fornyelsesområdet tilstrebe utbygging i området som fører til høyere områdetetthet og større grad av flerfunksjonalitet. I gjeldende reguleringsplan gir det samlet sett anledning til å tilrettelegge for ca. 200.000 kvadratmeter bruttoareal.

Sentrumsutvikling Ås og Tandbergkvartalet

Ifølge oversendt underlag skal Ås kommune høsten 2019 vedta områderegulering for Ås sentralområde. NMBU eier ca. 17% av Tandbergkvartalet.

«Planområdet ligger nord i Ås sentrum og er avgrenset av Raveien i vest og Brekkeveien i øst. Undergangen under Østfoldbanen avgrenser området i syd, og Fylkesvei 152 i nord. Planområdet utgjør om lag 12000 kvadratmeter i utstrekning. Nord i området ligger en høyde med et godt tilvokst skogholt. Store deler av området er i dag tatt i bruk som parkeringsplass, tilknyttet det eksisterende bygget i Raveien 9 hvor det er etablert dagligvarebutikk og kontorer». I innspill til områdereguleringsplan for Ås sentralområde spiller Reiulf Ramstad i Reiulf Ramstad Arkitekter inn at utnyttelsesgraden i sentrum bør ligge på 320%.

Oversikt	Gbnr	Hjemmelshaver	Andel
	42/307 42/122	Raveien 9 AS	40 %
	42/288	Tandberg	18 %
	42/1	NMBU	17 %
	55/52	Veidekke ASA	8 %
	55/53	Ås kommune	7 %
	55/524	Ås sentrum øst AS	6 %
	121/10 121/9	Akershus fylkeskommune og Statens Vegvesen	4 %

I oversendt prosjektbeskrivelse av Tandbergkvartalet 19.08.2019 fremgår det at kvartalet har et potensiale på 38 171 m^2 BRA kontor, næring, kultur, bolig, studentbolig, hotell/næring/bolig.

arealtabell

etasje	Tandberg	Veidekke	Raveien 9	BKB 4	BKB 1	NMBU
1	1555	1328	1312	544	793	847
2	1555	1328	1312	544	793	847
3	375	746	1312	544	665	670
4	375	746	839	544	550	670
5	375	746	839	544	550	580
6	375	746	839	544	550	580
7	375	746	839	544	550	580
8	375	526		360	550	580
9	375				550	580
10	375				378	580
11	375				196	
12	375					
13	200					
14	100					
BRA (m2)	7160	6912	7292	4168	6125	6514
Total BRA (m2)						38171

kontor
næring
kultur
bolig
student bolig
hotell/næring /bolig

Basert på oversikten fremgår det at ca. 65% er bolig, mens 45% er ulike næringstyper. Forenklet fordeler det seg slik:

	Tandberg	Veidekke	Raveien9	BKB4	BKB1	NMBU	Sum
Boligdel	4 050	4 256	3 356	3 624	6 125	3 480	**24 891**
Næringsdel	3 110	2 656	3 936	544	-	3 034	**13 280**
Sum	**7 160**	**6 912**	**7 292**	**4 168**	**6 125**	**6 514**	**38 171**

I denne rapporten gjør vi beregningene i brutto areal (BTA) og har derfor omgjort BRA til BTA med omgjøringsfaktor 0,92. Det tilsvarer 41 490 m^2 BTA totalt, hvorav 27 055 m^2 BTA bolig og 13 435 m^2 BTA næring.

Deler av 42/1 i sentrum

I Ås kommuneplan 2015-2027 er deler av 42/1 avsatt til kombinert bebyggelse og anlegg fremtidig.

Fra kommuneplan

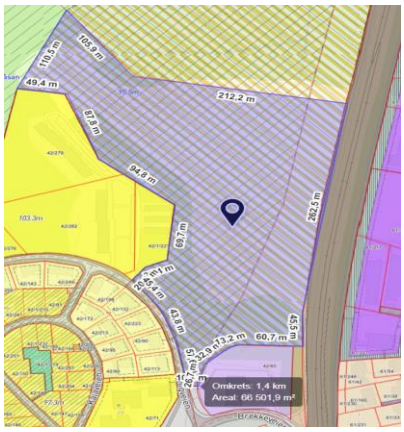

Oppmålt areal på g.nr/b.nr 42/1

Det gjelder ca. 66.5 daa. Området inngår i gjennomføringssone H810_2 «krav om felles planlegging» som sier at «*På Åsmåsan kreves reguleringsplan(er) for eiendommene 42/1 og 56/1*». I tillegg er eiendommen merket med hensynssone H570_2 «Bevaring av kulturmiljø» som sier «*Riving av bebyggelse eller større bygge- og anleggstiltak som forringer verdiene og hindrer bevaring av historiske trekk i landskap og bebyggelse, skal unngås*».

Ettersom eiendommen er beliggende i tilknytning til Ås sentrum anser vi at området vil sannsynligvis få en høy utnyttelse, men ettersom den er merket for hensynssone H570_2 vurderer vi det vil kunne komme noen begrensninger. Vi har skjønnsmessig lagt til grunn påregnelig utnyttelse på ca. 100% TU i dette området.

Området er kun avsatt til kombinert formål. Dersom vi antar 100% TU tilsvare det 66 500 m^2 BRA. Omgjort til 72 282 m^2 BTA. Ettersom det er ønskelig med kombinert bebyggelse har vi skjønnsmessig lagt til grunn 60/40 bolig og næring.

Brønnerud skole

Maks bebygd areal (BYA) er 20%, maks møneh. 11,5m og gesimsh. 8,5. Reguleringsområdet er iht. plankartet 21 daa. NMBU sin tomt er iht. oversendt oversikt 18,3 daa. Potensialet tilsvarer 9 150 m^2 BTA. Ifølge planbestemmelsene tillates det bebyggelse innenfor de byggegrenser, de byggehøyder og det bebygde areal planen viser. Basert på flyfoto er tomten tilsynelatende bygd ut i tråd med gjeldene regulering.

Ås gård
Areal og bygg innenfor feltene kan benyttes til: Landbruksformål med husdyrrom, fôrlager, gjødsellager, verksteder, forskning, undervisning, administrasjon og fellesfunksjoner. Publikumsrettet virksomhet for de fagfelt som har sin virksomhet i området, herunder besøksgård. Maksimal utnyttelsesgrad OP1: 31000 m2 BRA. Ifølge Nordeca Insight er området bebygd med ca. 16 250 m^2 BRA. De er derfor et potensial for ca. 15 000 m^2 BRA innenfor feltet.

LNF Areal
Korsegårdsmåsan, Hala gård, Berg, Kinn, Norderås og Bjørnebekk er LNF-områder. Det er til sammen 1 859,7 daa iht. oversendt eiendomsoversikt. Av NMBU hovedbruk har vi målt opp ca. 66,5 daa i sentrum som har annet formål enn LNF og planområdet på reguleringsplan Ås Campus er ca. 475 daa med offentlig formål. Det vil si at ca. 400 daa av dette området er LNF eller veiareal.

Samlet sett ansees ca. 2 250 daa av de vurderte 5 222 daa. å være LNF- formål basert på disse beregningene. Samlet sett vurderes verdien av landbruk og skogarealer å være marginal. Erfaringsmessig vil verdien normalt ligge på per kvadratmeter tomt mellom 1-20 kr. Prisen er avhengig av blant annet bonitet, kvalitet på dyrkbar mark og beite. I denne vurderingen har vi basert på liten samlet verdi, for enkelhet skyld lagt til grunn kr. 10 pr. m^2 for disse arealene

POTENSIALETS VERDI
Verdifastsettelse av tomter avhenger av bruksformål, beliggenhet, utbyggingspotensiale og forventet avkastning, vurdert som ubebygget tomt. Tomtebelastning er differansen mellom markedsverdi av fullt utbygd eiendom og totale byggekostnader inkl. fortjeneste, men ekskl. kostnader til opparbeidelse av tomt, fordelt pr. m^2 (BTA) bebygd gulvareal, ekskl. kjeller. I eiendommer hvor kjellerarealet utgjør en vesentlig verdi, skal dette fastsettes særskilt.

I mer perifere områder med større tomtetilgjengelighet regnes tomteverdier oftest som verdi pr. m^2 netto tomt og ikke tomtebelastning. Ved vurdering av tomteverdi vurderes også verdi pr. m^2 netto tomt, sett i relasjon til omsatte, sammenlignbare tomter.

I beregning av tomteverdi inngår både fortjeneste til grunneier for uregulert råtomt og verdiskapning i forbindelse med utvikling slik at tomten blir salgbar. Fortjenesten deles ofte mellom grunneier og tomteutvikler/utbygger i forholdet 50/50, og utvikler får betalt for den risiko som tas i forbindelse med f.eks. en omregulering. Dette endrer seg i utviklingsprosjekter med mer usentral beliggenhet og stor risiko, hvor grunneierandelen kan synke ned mot 10 % - 20 %. Ved prosjekter med liten risiko er tomteeiers andel av tomteverdien større. Utbyggere regner vanligvis med at tomtens verdi utgjør 10 % - 15 % av et ferdig prosjekts totalverdi. I pressområder kan dette være høyere.

Eiendomsverdi
Ifølge Eiendomsverdi.no er det solgt 4 leilighet og 9 eneboliger med byggeår 2017 - 2019 de siste 12 mnd. Ås. Salget av leilighetene utgjør kr. 79 000 pr. m^2 P-rom. Eneboligene utgjør kr. 58 000 pr. m^2 P-rom. Leilighetene er sentralt beliggende, noe som gjenspeiles i prisen.

Referanser finn.no

Vi har også undersøkt boliger til salgs i direkte nærhet til den vurderte eiendommen på Finn.no den 25.10.2019. Nedenfor er referansene nummerert og vist på kart:

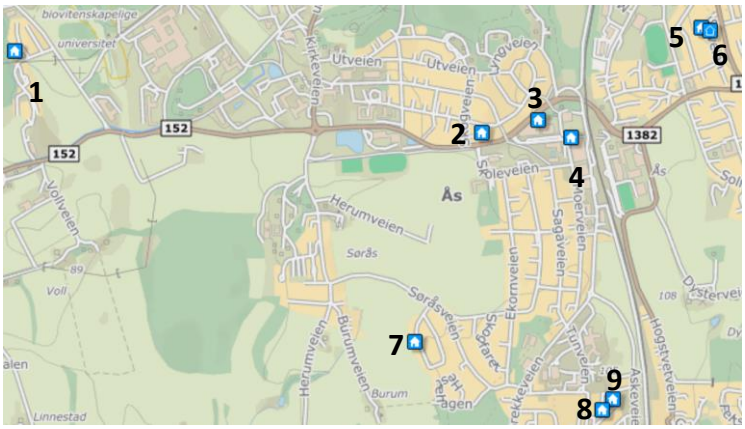

Tabellen oppsummerer informasjon om referansene:

Ref .nr.	Adresse	Boligtype	P-rom	Ant. soverom	Prisantydning	Pris/m2 P-Rom	Kommentar
1	Brynhilds vei 8	Enebolig	217	6	6 290 000	28 986	Oppusset i nyere tid, morderne overflater
2	Drøbakveien 19	Enebolig	189	4	7 990 000	42 275	Renoveringsobjekt. 2 daa tomt.
3	Raveien 10D	Leilighet	69	2	4 150 000	60 145	Byggeår 2014
4	Rådhusplassen 2 C	Leilighet	71	2	4 500 000	63 380	Byggeår 2007
5	Solveien 16	Enebolig	100	2	6 350 000	63 500	Renoveringsobjekt, 1.5 daa tomt
6	Solveien 17	Enebolig	173	4	8 850 000	51 156	Prosjekterte eneboliger
7	Landåskollen 13	Enebolig	222	4	8 000 000	36 036	Oppussingsobjekt, 1 daa tomt
8	Heggveien 41	Tomanns bolig	114	3	4 940 000	43 333	Byggeår 2011
9	Heggeveien 59	Tomanns bolig	114	3	5 000 000	43 860	Byggeår 2012

Basert på undersøkelsen viser at en enebolig vest for campus selges for ca. 29 000,- per m^2 P-rom. Huset fremstod basert på bilder som oppusset innvendig i nyere tid. Eneboligene nærmere sentrum ligger rundt 40 000-63 500,- per m^2 P-rom. To av disse var renoveringsobjekter med 1.5-2 daa tomte. Basert på salgsannonsen til referanse 5 i Solveien 16 oppgis det at eiendommen har utviklingspotensiale, og på annonsebildene fremgår det at det bygges nye boliger på nabotomtene. En enebolig sørvest for sentrum som selges for ca. 36 000,- per m^2 P-rom. Huset er fra 1974 og har i hovedsak ubehandlede panelvegger og kjøkken/bad som tilsynelatende er fra byggeår.

Ettersom vi omtaler boligutvikling sammen med næringsutvikling har vi valgt å oppgi disse i samme areal. Salgsprisene over er oppgitt i salgbart bruksareal (BRA-S)/primærrom (P-ROM). Næringseiendom oppgis normalt i bruttoareal (BTA) og vi vil videre omgjøre salgspriser og

byggekost på bolig til BTA. Ifølge en kjent boligutvikler i bygg.no(2016) regnes normalt bruksareal (BRA) å utgjøre 92% av BTA. Det salgbare bruksarealet (BRA-S) utgjør igjen 82% av BRA. Samlet tilsvarer forholdet mellom BRA-S og BTA ca. 75%.

Basert på lokalkunnskap og opplysninger om tidligere omsetninger fra Eiendomsverdi og Finn.no, har vi valgt å legge til grunn følgende salgsverdier:

Leilighet, kr. 70 000,- per m^2 BRA-S. Kr. 52 500,- per m^2 BTA

Rekkehus, kr. 57 000,- per m^2 BRA-S. Kr. 42 750,- per m^2 BTA

Salgsinntekter næringsbygg
For å beregne salgsverdi av næringsbygg på den vurderte eiendommen har vi benyttet kapitaliseringsmetoden. Metoden går ut på å dividere påregnelig netto årlig leieinntekt en eiendom kan oppnå med normale avkastningskrav i til investorer i markedet, også kalt yield. Netto leieinntekt er summen av brutto leieinntekt fratrukket antatt arealledighet og eierkostnader.

Brutto leieinntekt
For å anslå påregnelig brutto leieinntekt har vi sett på markedsrapporter. Det finnes tilgjengelige markedsrapporter som er utarbeidet av næringsmeglere. Vi har benyttet:

- Union Gruppens digitale markedsrapport
- Akershus Eiendom sin markedsrapport våren 2019

Det finnes lite markedsdata om institusjonsformål og undervisningsbygg, så vi har valgt å se på leienivåer for kontorbygg.

Næringsmegler	Område	Leie/m2/år for moderat standard	Leie/m2/år for høy standard	Leie/m2/år Toppleie
Union Gruppen	Ytre Syd	1 150	1 350 – 1 600	1 800
Akershus Eiendom	Out City South		1 200*	1 600

**Akershus Eiendom skiller mellom «General high standard og Top standard and new spaces»*

Basert på dette anslår vi en påregnelig brutto årlig leie på 1 700,- per m^2/BTA/år for nye næringslokaler.

Arealledighet
Ifølge Union Gruppen er det per februar 2019 4,2% kontorledighet i ytre syd. Ifølge Akershus Eiendom er ledigheten i ytre syd på mindre enn 7%. Vi forutsetter at det tegnes en langvarig kontrakt på 10 år eller mer og her derfor valgt å ikke medta arealledighet.

Eierkostnader
Ifølge Basalerapporten 2018 er de totale årlige eierkostnadene per m^2 mellom kr. 137-361,-. Vi har skjønnsmessig lagt til grunn 150,- per m^2 BTA for nybygg.

Yield
Ifølge Union Gruppen er Prime yield i ytre syd 5,10%. Ifølge Akershus Eiendom er prime yield i Oslo utenfor sentrum er 4,25%. Vi har skjønnsmessig lagt til grunn 5,50% yield for nye lokaler i Ås.

Kapitalisert verdi

Brutto leieinntekt	Arealledighet	Eierkostnader	Netto leieinntekt	Kapitaliseringsrente	Salgsverdi
1700	0 %	150	1 550	5,5 %	28 182

Avrundet salgsverdi for nytt næringsbygg er beregnet til kr. 28 000,- per m^2 BTA.

Byggekostnader bolig

Ifølge Norsk Prisbok er byggekostnader for de ulike leilighetstypene:

- Boligblokk plasstøpt betong med lukket p-kjeller Kr. 26 905,- per m^2 BTA inkl. mva.
- Boligblokk med svalgang og lukket P-Kjeller Kr. 28 591,- per m^2 BTA inkl. mva.
- Boligblokk prefab betong med lukket p-kjeller kr. 27 211,- per m^2 BTA inkl. mva.
- Rekkehus uten kjeller kr. 27 107,- per m^2 BTA inkl. mva.

Basert på overnevnte byggekostnader ser vi at disse ligger avrundet i spennet 27 000 – 28 500,- per m^2 BTA inkl. mva.

I disse kostnadene inngår:

- Felleskostnader (rigging, drift av byggeplass, byggeplassadministrasjon, prosjektering, kontroll og dokumentasjon, samt kapitalytelser)
- Bygging (Grunn og fundamenter, inner- og yttervegger, dekker yttertak, fast inventar, trapper, balkong mm. Og andre bygningsmessige deler)
- VVS-installasjoner, elkraft, tele og automatisering og andre installasjoner.
- Generelle kostnader (prosjektering, administrasjon, bikostnader, forsikring, gebyrer.
- Mva.
- Forventet tillegg, usikkerhetsavsetning.

For å sammenligne med salgspris, omgjøres pris per BTA til pris per BRA-S med samme omgjøringsfaktor som tidligere nevnt 0,75. Det tilsvarer mellom kr. 36 000 – 38 000,- per m^2 BRA-S. Som tidligere nevnt vil vi oppgi priser per BTA.

Ifølge bygg.no (2019) bygde Veidekke Grenselunden i Ås kommune for kr. 134 millioner eks mva. Prosjektet består av to boligblokker med et næringsareal (Kiwibutikk). Trinn 1 er et modulbygg på fire etasjer med en KIWI-butikk i første etasje, mens trinn 2 er et tradisjonelt byggeri på fem etasjer. Prosjektet oppgis til 8 431 m^2 BRA. Omgjort til BTA tilsvarer det 9 164,- per m^2 BTA. Det tilsvarer kr. 14 622,- per m^2 BTA eks mva. Inkl. mva. tilsvarer det kr. 18 278,- per m^2 BTA.

Byggekostnader næring

Ifølge Norsk Prisbok koster det mellom 24 285 – 31 655,- eks. mva. m^2 BTA for nye kontorbygg avhengig av standard og areal. Vi er kjent med prosjekter utenfor Oslo hvor byggekostnadene for kontorbygg ligger rundt kr. 20 000,- per m^2 BTA. Eksempelvis ifølge Bygg.no (2018) skal Constructa Entreprenør AS bygge Buebygget (kontorbygg) i Bergen for kr. 300 millioner eks. mva. (totalentreprise). Prosjektet er på ca. 14 500 m^2 BTA og skal utføres etter BREAAM Excellent-klassifisering. Det tilsvarer kr. 20 670,- per m^2 BTA. I samme artikkel fremgår det at Construcuta Entreprenør i dag bygger Vinkelbygget i samme området for kr. 250 millioner eks. mva. Prosjektet er på ca. 13 000 m^2 BTA. Det tilsvarer kr. 19 230,- per m^2 BTA.

Ifølge bygg.no (2019) har Veidekke fått i oppdrag av Fløybyen AS (heleid av Arendal kommune å bygge et miljøsertifisert kontorbygg på 6 100 m^2 BTA. Kontrakten er en totalentreprise verdt kr. 158

millioner eks. mva. Det tilsvarer kr. 25 901,- per m^2 BTA. Bygget får passivhusstandard og miljøsertifiseres etter BREEAM-NOR.

Ifølge buildingsupply.no (2019) bygger AF gruppen Os skole i Halden for kr. 405 millioner eks. mva. Kontrakten består av samhandling og utførelse av ny barne- og ungdomsskole for 660 elever, idrettsanlegg med håndball med to håndballflater, matchbane for eliteseriehåndball og en basishall. Totalt bruttoareal er 15 750 m^2 BTA. Det tilsvarer kr. 25 714,- per m^2 BTA.

Ifølge ingeniørfirmaet Malnes og Endresen på me.no (2019) fremgår det at det skal byges nytt Fjørfehus tilknyttet Ås gård Fjørfehuset bygges opp som et forsøkshus med separate hønserom, dissekeringsrom og kontorer for administrering og kontroll av forsøk. Prosjektet består av nytt fjørfehus på ca. 1 600 m^2 BTA på to etasjer. Kostnadsrammen er på ca. 35 millioner. Det tilsvarer kr. 21 875,- per m^2 BTA.

Basert på dette har vi noen referanser som ligger mellom 20-26 000,- per m^2 BTA.

Byggekostnadene for næringsbygg her vurderer vi vil ha en sammenheng mellom hva man forventer å oppnå i leienivå. Ettersom vi har lagt til grunn 1 700,- per m^2 BTA/år som er i øvre sjikt i området vurderer vi at det vil være markedsmessig å legge til grunn moderat standard. Vi har derfor valgt å legge til grunn gjennomsnittlig kvadratmeterpris på nye næringsbygg på kr. 20 000,- per m^2 BTA.

Infrastruktur
Kostnader til infrastruktur på eiendommen er normalt kostnader som kan knyttes til interne veier, veilys/parklys. Det kan også være lekeplasser, felles parkeringsplasser, parkarealer, avfallsanlegg mm. Ved større utbygninger kan kommunen sette krav til at utbygger betaler et infrastrukturbidrag for å dekke kostnader knyttet til økt behov for eksempelvis etablering av flere skoleplasser, barnehage, kollektivdekning, veier, plasser mm.

Kostnadene varierer, men erfaringsmessig ligger kostnaden på +/- kr. 1 500,- per m^2 BTA. I denne vurderingen har vi skjønnsmessig vurdert kostnaden til kr. 1 000,- per m^2 BTA

Byggeherrekostnader, finans, adm., prosjekt-/byggeledelse og gebyrer

Byggherrens kostnader til finansiering, administrasjon, prosjekt- og byggeledelse, samt gebyrer er ikke inkludert i Norsk Prisbok sine utregninger. Disse vurderer vi normalt å utgjøre 10 – 20 % av byggekostnadene. For hele planområdet har vi lagt til grunn 15%.

Potensialets verdi NMBU Hovedbruk CAMPUSDELEN
Ifølge våre beregninger kan det bygges inntil 500 000 m^2 BTA iht. gjeldene regulering. Dette er ca. 3x så mye som dagens bebyggelse. Ifølge NMBU (2014) har Campus vokst frem de siste 150 årene. Det vurderes derfor å ta lang tid å utvikle alle de regulerte kvadratmeterne i gjeldene plan. Det vil derfor være høy markeds- og tidsrisiko om det totale potensialets verdi er grunnlag for tomteverdien.

	Areal, BTA	Pris per m2	Sum
Gjennomsnittlig salgspris nybygg næring	500 000	28 000	14 000 000 000
Salgs- og markedsføringskostnader, 1,5 %	500 000	420	210 000 000
Netto salgspris	**500 000**	**27 580**	**13 790 000 000,00**
Byggekostnader for nybygg næring	500 000	20 000	10 000 000 000
Infrastrukturkostnader	500 000	1 000	500 000 000
Finanskostnader og gebyr, 15 %	500 000	3 150	1 575 000 000
Sum byggekostnader	**500 000**	**24 150**	**12 075 000 000**
Brutto tomteprisbelastning	**500 000**	**3 430**	**1 715 000 000**
Risiko/gevinst til utbygger, 80 %	**500 000**	2 744	1 372 000 000
Netto tomteprisbelastning	**500 000**	**686**	**343 000 000**

Sum netto tomteprisbelastning	500 000	686	343 000 000
Sum byggekostnader	500 000	24 150	12 075 000 000
Sum investert kapital	**500 000**	24 836	**12 418 000 000**
Risiko/gevinst til utbygger/investor i %			11,0
Direkteavkastning utbygger/investor	**500 000**	2 744	**1 372 000 000**

Planområdet er oppgitt til 475 daa. Deler av dette planområdet er allerede bebygd. Utbygningspotensialet er av en størrelse som vil ta meget langt tid å utvikle. Normal netto tomebelastning i området vurderes å ligge på rundt kr. 2500 som over en periode på tidsperiode på 20 år vil tilsi 135 000 – 140 000 m^2 BTA.

Potensialets verdi Tandbergkvartalet

I oversendt prosjektbeskrivelse av Tandbergkvartalet 19.08.2019 fremgår det at kvartalet har et potensiale på 38 171 m^2 BRA kontor, næring, kultur, bolig, studentbolig, hotell/næring/bolig. Vi har tidligere synliggjort fordelingen av dette i en tabell, hvor det fremgår at ca. 65% av dette er bolig og 45% er ulike typer næring. I denne rapporten gjør vi beregningene i brutto areal (BTA) og har derfor omgjort BRA til BTA med omgjøringsfaktor 0,92. Det tilsvarer 41 490 m^2 BTA totalt, hvorav 27 055 m^2 BTA bolig og 13 435 m^2 BTA næring.

	Areal, BTA	Pris per m2	Sum
Gjennomsnittlig salgspris for bolig	27 055	52 500	1 420 387 500
Gjennomsnittlig salgspris næring	13 435	26 500	356 027 500
Salgs- og markedsføringskostnader, 1,5 %	40 490	658	26 646 225
Netto salgspris	**40 490**	**43 215**	**1 749 768 775,00**
Byggekostnader for bolig	27 055	30 000	811 650 000
Byggekostnader for næring	13 435	20 000	268 700 000
Infrastrukturkostnader	40 490	1 000	40 490 000
Finanskostnader og gebyr, 15 %	40 490	4 152	168 126 000
Sum byggekostnader	**40 490**	**31 834**	**1 288 966 000**
Brutto tomteprisbelastning	**40 490**	**11 381**	**460 802 775**
Risiko/gevinst til utbygger, 50 %	**40 490**	4 552	184 321 110
Netto tomteprisbelastning	**40 490**	**6 828**	**276 481 665**
NMBU sin andel	17 %		**47 001 883**

Sum netto tomteprisbelastning	40 490	6 828	276 481 665
Sum byggekostnader	40 490	31 834	1 288 966 000
Sum investert kapital	**40 490**	38 663	**1 565 447 665**
Risiko/gevinst til utbygger/investor i %			11,8
Direkteavkastning utbygger/investor	**40 490**	4 552	**184 321 110**

NMBU sin andel utgjør 17% av prosjektet. Det tilsvarer totalt (avr.) kr. 47 000 000,- Tomtearealet til NMBU utgjør ca. 2 500 m^2 basert på oppmåling på kart, som tilsvarer kr. 18 800,- per m^2 tomt. Prosjektet er beliggende midt i Ås sentrum nær stasjonen og legger opp til en høy utnyttelse på 320% ifølge innspill til områdereguleringsplan for Ås sentralområde av Reiulf Ramstad Arkitekter.

Potensialets verdi Ås gård

Areal og bygg innenfor feltene kan benyttes til: Landbruksformål med husdyrrom, fôrlager, gjødsellager, verksteder, forskning, undervisning, administrasjon og fellesfunksjoner. Publikumsrettet virksomhet for de fagfelt som har sin virksomhet i området, herunder besøksgård. Disse formålene vurderes å ha lavere byggekostnader og lavere salgsverdi. Vi har funnet en referanse på byggekostnader på et forsøksbygg på området for kr. 22 000,- per m^2 BTA. Basert på befaring var det en del enklere bygg enn dette og vi antar derfor at den generelle byggekostnaden i feltet vil være lavere per kvadratmeter.

	Areal, BTA	Pris per m2	Sum
Gjennomsnittlig salgspris nybygg næring	15 000	20 000	300 000 000
Salgs- og markedsføringskostnader, 1,5 %	15 000	300	4 500 000
Netto salgspris	**15 000**	**19 700**	**295 500 000,00**
Byggekostnader for nybygg næring	15 000	15 000	225 000 000
Infrastrukturkostnader	15 000	1 000	15 000 000
Finanskostnader og gebyr, 15 %	15 000	2 400	36 000 000
Sum byggekostnader	**15 000**	**18 400**	**276 000 000**
Brutto tomteprisbelastning	**15 000**	**1 300**	**19 500 000**
Risiko/gevinst til utbygger, 60 %	**15 000**	650	9 750 000
Netto tomteprisbelastning	**15 000**	**650**	**9 750 000**

Sum netto tomteprisbelastning	15 000	650	9 750 000
Sum byggekostnader	15 000	18 400	276 000 000
Sum investert kapital	**15 000**	19 050	**285 750 000**
Risiko/gevinst til utbygger/investor i %			3,4
Direkteavkastning utbygger/investor	**15 000**	650	**9 750 000**

Planområdet er oppgitt i reguleringsplanen til 73,9 daa. Tomteverdien tilsvarer dermed 132,- per m^2 tomt.

Potensialets verdi deler av 42/1 i sentrum

Dersom vi antar 100% TU tilsvare det 66 500 m^2 BRA. Omgjort til 72 282 m^2 BTA. Ettersom det er ønskelig med kombinert bebyggelse har vi skjønnsmessig lagt til grunn 60/40 bolig og næring. Området er kun avsatt til kombinert formål, og vi vurderer derfor at det er høy reguleringsrisiko knyttet til prosjektet. Dette gjenspeiles i risiko/gevinst til utbygger.

	Areal, BTA	Pris per m2	Sum
Gjennomsnittlig salgspris for bolig	43 369	42 750	1 854 024 750
Gjennomsnittlig salgspris næring	28 913	28 000	809 564 000
Salgs- og markedsføringskostnader, 1,5 %	72 282	553	39 953 831
Netto salgspris	**72 282**	**36 297**	**2 623 634 918,75**
Byggekostnader for bolig	43 369	28 000	1 214 332 000
Byggekostnader for næring	28 913	20 000	578 260 000
Infrastrukturkostnader	72 282	1 000	72 282 000
Finanskostnader og gebyr, 15 %	72 282	3 870	279 731 100
Sum byggekostnader	**72 282**	**29 670**	**2 144 605 100**
Brutto tomteprisbelastning	**72 282**	**6 627**	**479 029 819**
Risiko/gevinst til utbygger, 50 %	**72 282**	3 314	239 514 909
Netto tomteprisbelastning	**72 282**	**3 314**	**239 514 909**

Sum netto tomteprisbelastning	72 282	3 314	239 514 909
Sum byggekostnader	72 282	29 670	2 144 605 100
Sum investert kapital	**72 282**	32 984	**2 384 120 009**
Risiko/gevinst til utbygger/investor i %			10,0
Direkteavkastning utbygger/investor	**72 282**	3 314	**239 514 909**

Netto tomtebelastning utgjør totalt (avr.) kr. 239 500 000,-. Tomtearealet utgjør ca. 66 500 m^2, som tilsvarer kr. 3 600,- per m^2 tomt.

Samlet verdi tomtenes potensial

Regulert område	Beregnet verdi
Campus	343 000 000
Tandbergkvartalet, NMBU sin andel	47 000 000
Ås Gård	9 750 000
Del av 42/1 nær Ås sentrum, kombinasjon	239 500 000
Sum	**639 250 000**

Sum avrundes til kr. 639 000 000

LNFR-areal

LNFR-arealet utgjør ca. 2 250 daa og består av både landbruksjord og tettvokst skog. Verdien av arealer avsatt til LNFR ligger normalt i spennet kr. 1 – 20.

Videre har vi skjønnsmessig lagt til grunn kr. 10 per kvm tomt som tilsvarer kr. 22 000 000

Teknisk verdi tomt

Teknisk verdi tomt er verdien av tomtegrunnen fratrukket potensialets verdi og verdi for LNFR. Teknisk verdi tomt er beregnet ved å multiplisere netto tomtebelastning med Bruttoareal bygg. Beregningen vises i vedlagt Excel-skjema.

Samlet for alle områdene er teknisk verdi tomt beregnet til kr. 338 597 304, som avrundes til kr. 339 000 000

Oppsummert tomteverdi

Samlet tomteverdi er beregnet til kr. 639 000 000 + 22 000 000 + 339 000 000 = kr. 1 000 000 000

Referanser

I Metra Næringsmegling sitt kundemagasin selges det en opparbeidet næringstomt i Myrer Skog industriområde, adresse Karistuveien 4 i Spydeberg. Tomten er 7 222 m^2 og selges for 6 mill. Det tilsvarer kr. 830,- per m^2 tomt.

Ifølge Estate nyheter (2015) kjøpte en tomt hvor den gamle yrkesskolen på Kaldnes på Nøtterøy ligger for kr. 75 millioner. Planen er at de eksisterende byggene skal rives og 250 nye boenheter settes opp. Basert på Obos sine nettsider ligger tomten i Banebakken 35 på g.nr/b.nr 1003/169 som er 33.5 daa. Det tilsvarer kr 2 239,- per m^2 tomt. Reguleringsplanen trådde i kraft 03.02.2016. Planens hensikt er ifølge planbestemmelse §1 «*Hensikten med planen er å legge til rette og gi rammer for transformasjon av området fra offentlig skoleområde til sentrumsnær bolig- og næringsbebyggelse*».

Bebyggelse

Ifølge Campusplanen består Campus Ås med Ås gård i 2018 av om lag 100 bygning på ca. 140 000 m^2 BTA, samt Samlokaliseringsprosjektet som er under bygging. Bygningene på campus varierer mye i alder og standard. Bygningsmassen har ulik kapasitet for ombygging. NMBU har mye arealkrevende forsknings- og utdanningsinfrastruktur som følge av nasjonale oppgaver. Eksempelvis Ås gård med senter for husdyrforsøk, senter for klimaregulert planteforskning, dyreklinikker, fiskelaboratorium m.m. Dette gjør at universitetet ligger høyt i snitt når det gjelder areal per ansatt og student.

Campusoversikt:

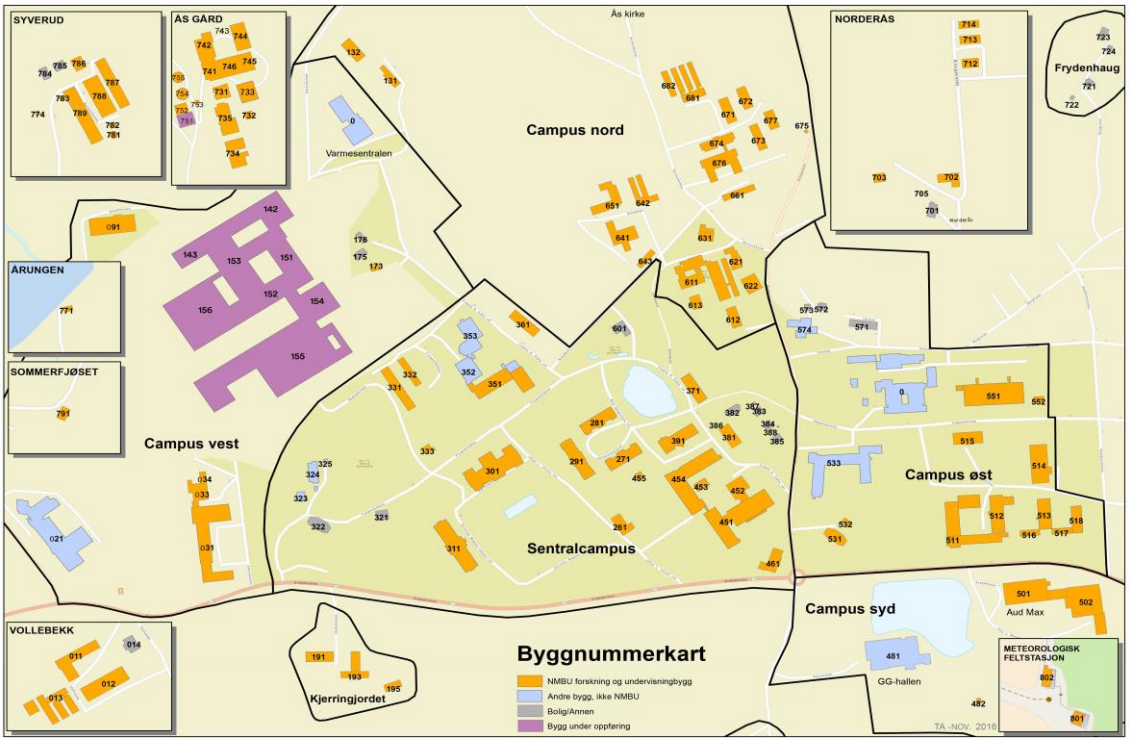

Basert på oppstartsmøte 16.10.2019 er ikke eiendommene på Syverud inkludert i vurderingen. I tillegg er det vurdert noen eiendommer på Slørstad som ikke fremgår av oversikten.

Byggenes tilstand

Ifølge campusplanen fremgår det at gjennomsnittlig tilstandsgrad for byggene i 2014 var på 1,8 og var i 2017 på 1,5. Målet til NMBU er 1,1. Når Samlokaliseringsprosjektet er ferdigstilt i 2020 er gjennomsnittlig tilstandsgrad forventet å være 0,92.

Fordeling av NMBUs bygninger på tilstandsklasser 2020				
Tilstandsklasse	T0	T1	T2	T3
Fordeling %	49%	12%	37%	2%

På kartet under ser vi oversikt over byggene som er tidligere vurdert med god, dårlig eller ille tilstand:

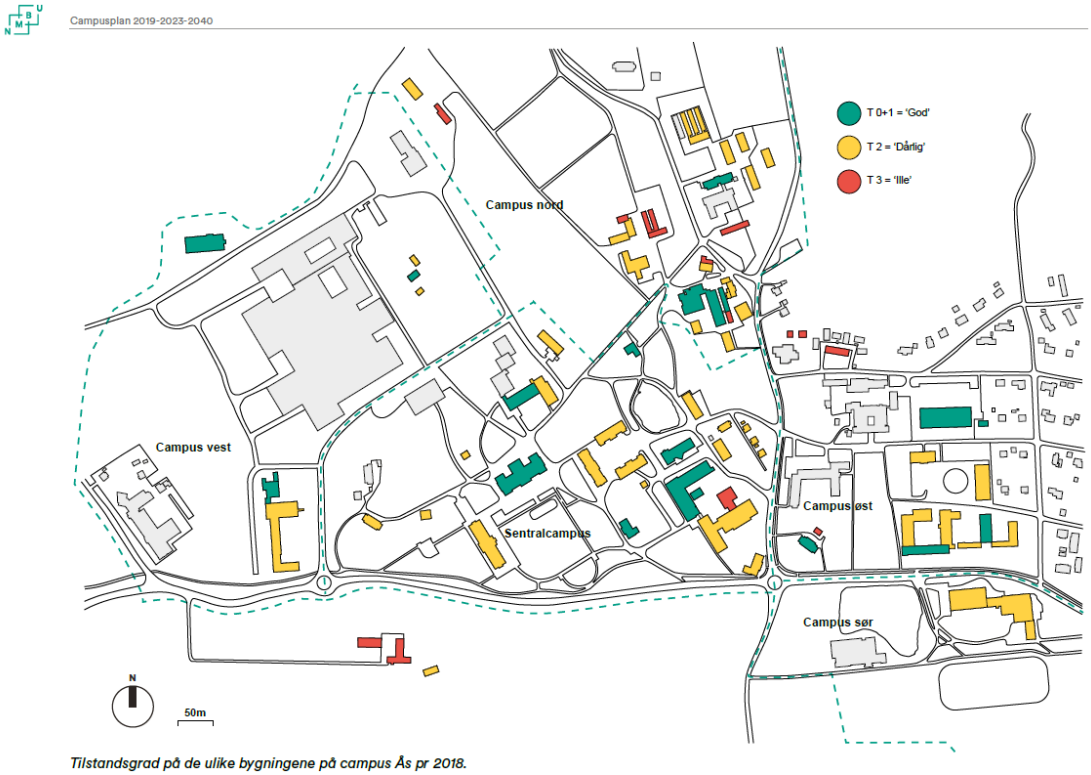

Tilstandsgrad på de ulike bygningene på campus Ås pr 2018.

I campusplanen fremgår det at i perioden 2018-2023 vil NMBU investeres ca. 650millioner kroner i utvikling, oppgradering og vedlikehold av bygninger og areal. For perioden etter 2023 er følgende større rehabiliterings- og oppgraderingsprosjekter prioritert:

- Totalrehabilitering av tunbygningene, Meierimuseet og Fruktkonserveringen
- Oppgradering av areal for forskningsfasiliteter for planteforskning og tilhørende studentarealer
- Oppgradering av Tårnbygningen
- Innovasjonsfasiliteter på campus Ås
- Totalrehabilitering av Meieribygningen
- Ombygging av Varmesentralen til studiearealer
- Sanering/erstatning Fløy 2-5 inkludering øvingsfløy i TF-kvartalet
- Større investeringer i utbedring av park og uteanlegg.

Frede bygninger

I oversendt underlag fremgår følgende opplysninger om vern:

Byggnavn	Oppført	Bygningsnr.	Gnr/bnr	Omfang
•Aud Max	1969 - 1970	149078304	42/1	Eksteriør/Interiør
•Botanisk klimalaboratorium	1962	149076093	42/1	Eksteriør
•Cirkus	1859 - 1902	149076018	42/1	Eksteriør/Interiør
•Damsgård, Kirkeveien 1	1899	149078290	42/1	Eksteriør/Interiør
•Fruktkonserveringa	1901	149076123	42/1	Eksteriør
•Gartnerboligen, Åsbakken 3/5	1887 - 1888	149076077	42/1	Eksteriør/Interiør
•Lindemannhuset, Fougnerbakken 16	1899	149075747	42/1	Eksteriør/Interiør

•Meieribygningen	1949 - 1953	149076204	42/1	Eksteriør/Interiør
•Meierimuseum, Kirkeveien 2	1900 - 1901	149078282	42/1	Eksteriør
•Palasset	1859	149076190	42/1	Eksteriør
•Palmyra, Fougnerbakken 18-20	1898 - 1899	149075720	42/1	Eksteriør/Interiør
•Parkgården	1866 - 1867	15374330	42/1	Eksteriør
•Smia	1859	149076182	42/1	Eksteriør/Interiør
•Stabburet	1859	149076034	42/1	Eksteriør/Interiør
•Tivoli	1859 - 1902	149075992	42/1	Eksteriør/Interiør
•Tårnbygningen	1921 - 1925	149075984	42/1	Eksteriør/Interiør
•Urbygningen	1898 - 1900	149075976	42/1	Eksteriør/Interiør
•Utomhus	1864 - 1951		42/1	Utomhus
•Økonomibygningen	1897	149076026	42/1	Eksteriør/Interiør

Ifølge campusplan er følgende bygningsmasse og parker fredet:

Fredet park og bygningsmasse.

I campusplanen fremgår det at 18 bygninger og 160 daa park er fredet etter kulturminneloven gjennom Landsverneplanen for Kunnskapsdepartementet.

Beskrivelse av bygg

Vi har valgt å dele inn områdene etter inndelingen i oversendt oversikt. Ettersom eiendommen består av ca. 100 bygg har vi valgt å gi en generell beskrivelse av hovedkonstruksjoner, overflater og tekniske installasjoner først og deretter en mer spesifikk beskrivelse av bygningsmassen, med hensyn på alder og formål fordelt på hvert område.

Konstruksjoner

Bygningsmassen er bygget etter vanlig byggeskikk på byggetiden. Husene er oppført i mur, betong, tre og stål. Fasadematerialet variere med byggeår og type bygg.

Fasader

De største og eldste byggene er med spekket tegl som er en del av den bærende ytterveggen. Enkelte mindre bygg er kledd med teglforblending, platekledning, trepanel el.

Yttertak

Yttertakene for de største byggene er tekket med skifter. Øvrige bygg har annen taktekking som asfalt takbelegg og takstein.

Overflater

Innvendige overflater varierer noe, men enkelte materialer er går igjen. På gulvene er det hovedsakelig benyttet linoleumsbelegg og dels gulvfliser. Enkelte arealer kan ha tregulv, parkett og lignende materiale. Veggene er for det aller meste pusset og malt. Malt trepanel i enkelte arealer. Himling er både nedsenket systemhiming og malte flater, enten malt murpuss, platekledning eller trepanel.

Tekniske installasjoner

Byggene har variasjon av tekniske installasjoner. Branntekniske installasjoner som omfatter brannvarslingsanlegg og nødlys og er tilsynelatende oppgradert og oppdatert etter nyere standard for store deler bygningsmassen. Type ventilasjon og løsning for luftbehandling varierer, men det som går igjen er mekanisk og termisk ventilasjon. El og VVS-anlegget har stor variasjon i alder og type utstyr og er tilpasset bruke av lokalene.

Boligbygg

Det ble ikke gitt tilgang til boligene og besiktigelsen ble derfor kun foretatt fra utsiden. Beskrivelsen av byggene er derfor kun basert på alder og utvendig besiktigelse. Mesteparten av bolighusene er oppført på begynnelsen av 1900-tallet (nærmere angitt for hvert delområde)

Ut i fra faglig bedømmelse og opplysninger om byggeår er bolighusene oppført med bærekonstruksjoner i tre, antakelig tømmerkasse, eller med stående plank som var vanlig i byggeperioden. På midten av 1900-tallet var det mer vanlig med «tungt» bindingsverk. Fasadene er kledd med stående og liggende trepanel. Yttertakene er tekket med for det meste betongtakstein. Annen taktekking kan forekomme.

Sentralcampus

Sentralcampus består av til sammen 29 bygg. Mesteparten av bygningsmassen benyttes til undervisning, forskning/kontor, men det er også flere boligbygg i området. Fordelt etter formål blir fordelingen slik:

- 20 bygg - Undervisning-/forskning-/kontor
- 9 bygg - Bolig

De eldste byggene er oppført på 1850-tallet. Senere ble det oppført flere bygg fra år 1900 og frem til 1960-tallet. Det nyeste bygget er som er tilført området ble oppført i 2002. Boligbyggene ble oppført i begynnelsen av 1900-tallet.

Campus øst

Campus Øst består av til sammen 15 bygg. Mesteparten av bygningsmassen benyttes til undervisning/forskning/kontor, men det er også noen lager for undervisningsutstyr og boligbygg i området. Fordelt etter formål blir fordelingen slik:

- 7 bygg – Undervisning/forskning/kontor
- 5 bygg – Lager
- 3 bygg – Bolig

Det eldste bygget som er et boligbygg ble oppført på 1860-trallet. Senere ble det i tillegg oppført et boligbygg + uthus og 2 bygg sør/vest i området som i dag benyttes til undervisning /forskning /kontor og utstyrslager. Bebyggelsen øst i området består av både undervisning/forskning/kontor og lager, oppført i perioden fra 1960-tallet og frem til 1980.

Campus syd

Campus Syd består av til sammen 3 bygg. Aud Max-bygget er sammensatt av 2 bygg. Det tredje bygget er et boligbygg.

Fordelt etter formål blir fordelingen slik:

- 1 bygg – Undervisning/forskning (Aud Max)
- 1 bygg – Undervisning/studentaktiviteter (Aud Max)
- 1 bygg – Bolig

Det eldste bygget som er et boligbygg ble oppført rundt 1920. Aud Max bygget er sammensatt av 2 bygg hhv. oppført i 1934 og 1970.

Campus Vest

Campus Vest består av til sammen 7 bygg (ikke medregnet bygg under oppføring). Bygningen syd i området er sammensatt av 3 bygg. Øst i området er det en boligbygg og lager, nord/vest ligger et forskningsbygg med akvarieaktivitet.

Fordelt etter formål blir fordelingen slik:

- 2 bygg – Undervisning/forskning/kontor
- 1 bygg – Undervisning/forskning/akvarie
- 2 bygg – Lager
- 2 bygg – Bolig og uthus

Det sammensatte bygget syd i området er opprinnelig fra 1962 og senere tilbygget i 1995. Samlingen av bolig, uthus og lager øst i området er fra tidlig 1900-tallet og 1950. «Akvariebygget» ble oppført i 1989.

Campus Nord

Campus Nord består av til sammen 22 bygg. Mesteparten av bygningsmassen knytter seg til forskning i gartneri (veksthus).

Fordelt etter formål blir fordelingen slik:

- 1 Undervisning/forskning/kontor/gartneri (hovedbygning)
- 2 Lager/garasje/verksted
- 18 Undervisning/forskning/kontor/gartneri

Det eldste bygget er oppført i år 1902. Feltet ble senere bygget ut først på 1930-tallet. I 1950, -60 og -70 tallet ble mye av gartneribebyggelsen oppført. Det siste bygget ble oppfør i 1992 og senere ble det etablert et større brakkebygg på feltet, byggeåret er ukjent.

Meteorologisk feltstasjon

Feltet består av 2 stk. feltstasjoner oppført og etablert i 1980.

Vollebekk

Vollebekk består av til sammen 4 bygg. Det eldste bygget er opprinnelig et boligbygg fra 1895 som benyttes som kontor. Resterende bebyggelse består av driftsbygg og veksthus og benyttes til forskning. Byggene er oppført hhv. i 1969 og 1975.

Sommerfjøset

Sommerfjøset består av ett bygg. Bygget er et gårdsbygg/driftsbygg oppført i 1990.

Årungen

Årungen består av ett bygg. Bygget er et pumpehus oppført i 1985.

Ås Gård

Ås Gård er et nyetablert felt bestående av til sammen 15 bygg, hvor hoveddelen er driftsbygninger for husdyr og gårdsdrift. Vest i området er det oppført et lagerbygg/garasje for større landbruksmaskiner, utstyr og diverse. 3 av byggene i samme område er runde tanker som benyttes til gjødsel og fôr. Hele feltet As Gård ble etablert og bygget ut i 2014. De siste byggene ble satt opp i 2016.

Norderås

Norderås består av til sammen 7 bygg. Det eldste bygget er opprinnelig et boligbygg fra 1895. Øvrige bygg er eldre driftsbygninger oppført i perioden fra 1950 – 1980. Byggene benyttes blant annet som lager, verksted og kontor. Et av byggene leies ut til kunstnere.

Slørstad

Slørstad er et inngjerdet område bestående av 3 garasjebygg/rekker i en etasje på bakkeplan. Et av byggene er av nyere dato, de to andre av eldre dato. Byggeårene er ukjent.

Frydenhaug

Frydenhaug består av til sammen 4 bygg. Det ene bygget er et boligbygg fra 1920. Det andre et uthus oppført i 1970. Resterende bygg er bolighus/speiderhus oppført i 1920 og som benyttes som samlingsplass for en speiderforening.

1. Teknisk verdi

Iht. mandat skal vi i første ledd vurdere den tekniske verdien av bebyggelsen. Måten vi har beregnet teknisk verdi på er basert på nybyggkostnad for de ulike byggene deretter har vi gjort fradrag basert på elde, slitasje og utidsmessighet.. Vi har mottatt underlag som sier noe om tilstandsgraden til de ulike byggene. Denne informasjonen har vi sett i sammenheng med hva vi har registrert på befaring og deretter foretatt et skjønnsmessige fradrag.

Byggekostander

Norsk prisbok sine kostnader for bolig

Ifølge Norsk Prisbok er byggekostnader for de ulike boligtypene:

- Enebolig med uinnredet kjeller, enkel standard kr. 22 434,- per m^2 BTA inkl. mva.
- Enebolig med uinnredet kjeller, normal standard kr. 24 075,- per m^2 BTA inkl. mva.
- Enebolig uten kjeller, normal standard kr. 29 390,- per m^2 BTA inkl. mva.

Basert på overnevnte byggekostnader ser vi at disse ligger avrundet i spennet 22 400 – 29 400,- per m^2 BTA inkl. mva.

I disse kostnadene inngår:

- Felleskostnader (rigging, drift av byggeplass, byggeplassadministrasjon, prosjektering, kontroll og dokumentasjon, samt kapitalytelser)
- Bygging (Grunn og fundamenter, inner- og yttervegger, dekker yttertak, fast inventar, trapper, balkong mm. Og andre bygningsmessige deler)
- VVS-installasjoner, elkraft, tele og automatisering og andre installasjoner.
- Generelle kostnader (prosjektering, administrasjon, bikostnader, forsikring, gebyrer.
- Mva.
- Forventet tillegg, usikkerhetsavsetning.

Norsk prisbok sine kostnader for relevante typer næringsbygg

Norsk Prisbok oppgir følgende byggekostnader på kontor/forretningsbygg/lager:

- Kjøpesenter/varehus i 1 etasje uten kjeller 2 400 m^2 BTA, Kr. 19 097,- per m^2 BTA eks. mva.
- Kontorbygg 15 000 m^2 BTA med kjeller, kr. 24 285,- per m^2 BTA eks. mva.
- Isolert lager lav 1 500 m^2 BTA, kr. 11 411,- per m^2 BTA eks. mva.

Beregning av teknisk verdi

Vi har utarbeidet et regneark i Excel for å beregne teknisk verdi. Utgangspunktet for den tekniske verdien er nybyggkostnadene for de ulike type bygningene ganget med antall kvadratmeter, deretter fradrag for elde, slitasje og utidsmessighet.

Basert på byggenes alder og tilstand har vi gjort fradrag for å beregne dagens tekniske verdi. Vi har vurdert at byggene kan fradragsføres med følgende prosenter:

TG 0 bygg vil fradragsføres mellom 0 – 10 %
TG 1 bygg vil fradragsføres mellom 10 – 40 %
TG 2 Bygg vil fradragsføres mellom 40 – 80 %
TG 3 bygg vil fradragsføres mellom 80 -100 %

Kostnadsdekkende leie

Begrepet «Kostnadsdekkende leie» kan ha ulike betydninger, men vi mener her den leien en leietaker må betale for å dekke de kostnadene utleier må dekke for å kunne stille tilgjengelig lokaler

for leietaker. Kostander som inkluderes i leien er; kapitalkostnader, kostander til forvalting drift og vedlikehold (FDV) og dekningen av forventet verdiendring for eiendommen.

Den kostnadsdekkende husleien ligger normalt mellom 5% og 8 % av investeringen eller eiendommens kostnad/verdi. Vi er også kjent med at %-satsen kan ligge over 8%

For eiendommene på ås har vi skjønnsmessig valgt å legge til grunn 7 % av teknisk verdi.

Ettersom det er mange bygg i vurderingene har vi valgt å legge ved beregningene som vedlegg og oppgi de beregnede verdiene oppsummert her:

Område	Areal	Teknisk verdi bygg	Teknisk verdi tomt	Teknisk verdi bygg + tomt	Teknisk verdi pr. kvm	Årlig leie	Gj. Sn. Leie Teknisk	Tomtepris belastning
Sentral campus	64 569	791 887 887	161 421 276	953 309 162	14 764	66 731 641	1 034	2500
Campus Syd	6 008	53 620 059	15 020 128	68 640 187	11 425	4 804 813	800	2500
Campus Øst	24 645	310 352 399	61 613 493	371 965 892	15 093	26 037 612	1 056	2500
Campus Vest	11 779	132 968 104	29 448 408	162 416 513	13 788	11 369 156	965	2500
Campus Nord	14 046	97 484 901	35 115 992	132 600 892	9 440	9 282 062	661	2500
Ås Gård	13 709	183 876 590	20 563 302	204 439 892	14 913	14 310 792	1 044	1500
Årungen	90	325 080	90 300	415 380	4 600	29 077	322	1000
Sommerfjøset	227	2 043 000	227 000	2 270 000	10 000	158 900	700	1000
Vollebekk	4 860	54 691 100	7 289 250	61 980 350	12 754	4 338 625	893	1500
Norderås	3 469	36 152 880	5 203 155	41 356 035	11 922	2 894 922	835	1500
Frydenhaug	382	4 060 800	513 000	4 573 800	11 973	320 166	838	1500
Slørstad	2 092	2 510 400	2 092 000	4 602 400	2 200	322 168	154	1000
Sum Ås	**145 876**	**1 669 973 199**	**338 597 304**	**2 008 570 503**	**13 769**	**140 599 935**	**964**	**2 321**

2. Markedsverdi

Iht. mandat skal vi i andre ledd vurdere markedsverdien av bebyggelsen. Som utgangspunkt for leieverdien har vi sett på teknisk verdi og ansett en kostnadsdekkende husleie som en faktor % av teknisk verdi. Dette har vi valgt å kontrollere med markedsdata. Basert på dette har vi fastslått en markedsmessig leie som gir grunnlag for å beregne avkastningsverdien til eiendommen.

Markedsforhold

For å få et inntrykk av markedet for slike eiendommer har vi undersøkt ulike kilder.

Markedsrapport

Det finnes tilgjengelige markedsrapporter som er utarbeidet av næringsmeglere. Disse konsentrerer seg i hovedsak om de fire største byene i Norge. Metra næringsmegler er en næringsmegler i Østfold og Follo som skriver på sine nettsider «*Eiendomsmarkedet i Oslo er i dag oversiktlig med tall og fakta, takket være kvartalsrapporter fra flere av de større meglerhusene. I resten av landet er det lite systematisk oversikt over leienivåer, prosenttall ledighet og utviklingstrender*.» De skriver videre at de skal starte med Metrarapporten, som kommer ut først i Q1 i 2020.

I denne vurderingen har vi derfor sett på markedsrapporter fra Oslo

Kontorleie

Union Gruppen sin markedsrapport høsten 2019 oppgir leienivåer og prime yield for kontor i ulike områder i Oslo. Mest nærliggende er «ytre syd»:

Ytre syd	
Prime yield	5,10 %
Leiepriser	
Toppleie	1 800
Høy standard	1 600 - 1 350
Moderat standard	1 150
Kontorledighet per oktober 2019	4,2 %
Nybygging (2019 - 2021)	6 500 m²
Markedsandel utleid areal	2 %

I Akershus Eiendom sin markedsrapport våren 2019 fremgår følgende leienivåer for kontor:

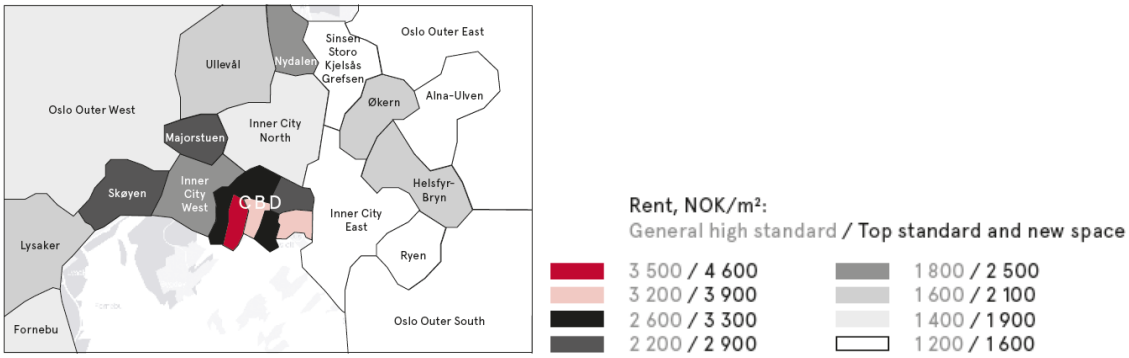

Her fremgår det at kontorleien for Oslo Outer South ligger på kr. 1 200,- per m² BTA/år for «general high standard» og kr. 1 600,- per m² BTA/år for «top standard and new space».

Lagerleie

Når det gjelder lagerleie oppgir Union Gruppen følgende:

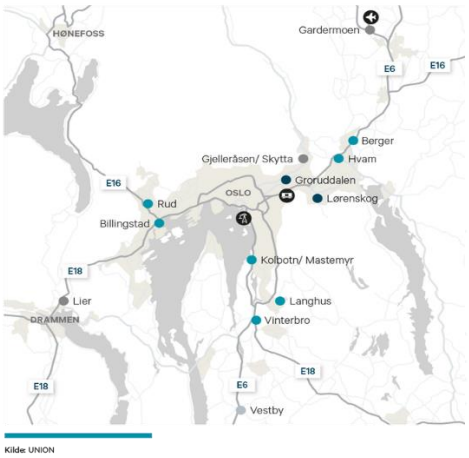

	Normal/høy standard[1]	Topp standard[2]
●	800 - 1 000	1 250
●	700 - 900	1 100
●	700 - 900	1 000
●	500 - 700	800

[1]Typisk nivå for gode lokaler med takhøyde inntil seks meter

[2]Lokaler med topp standard og takhøyde over seks meter

Mest nærliggende er Vestby, hvor lagerleien normalt ligger på mellom kr. 500-700,- per m² BTA/år og toppleie på kr. 800,- per m² BTA/år.

I Akershus Eiendom sin markedsrapport våren 2019 fremgår følgende leienivåer for lager:

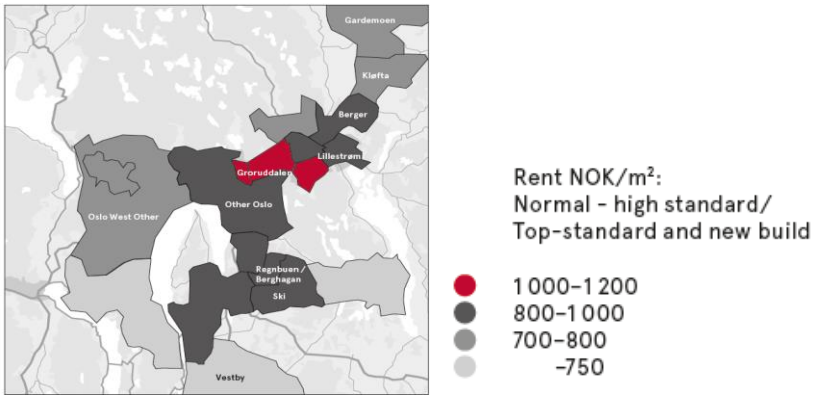

I Vestby fremgår det at lagerleien ligger på inntill kr. 750,- per m² BTA/år.

Leienivå ifølge Metra Næringsmegling

I Metra Næringsmegling sitt siste kundemagasin leies det ut ca. 1 500 m² lager og ca. 200 m² og kontor i Vålerveien 180 i Moss. Megler oppgir at leien for kontordelen ligger på kr. 950 per m² BTA/år og lagerdelen ligger på kr. 750,- per m² BTA/år. I samme kundemagasin leies en lager/logistikkbygg i Treveien 9 i Vestby ut for kr. 950,- per m² BTA/år. Eiendommen er på 5 339 m² BTA, hvorav ca. 80% er lager og 20% er kontor. Eiendommen ligger 5 min fra E6 i Vestby Næringspark.

Boligleie basert på Finn.no 28.10.2019

Eneboliger

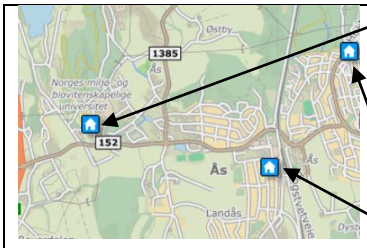	Det leies ut et hus i Drøbakveien 331 på campus Ås for kr. 12 000,- per mnd. Huset har 3 soverom og et P-rom på 115 m². Bruttoarealet er 125 m². Huset har eldre standard basert på bilder.
	I Torderudveien 33 leies det ut en enebolig for kr. 18 000,- per mnd. Huset har 4 soverom og et P-rom på 125 m². Huset har moderat standard basert på bilder.
	I Sagaveien 4B leies det ut et hus for kr. 21 000,- per mnd. Huset har 3 soverom og et P-rom på 117 m². Huset har moderat standard basert på bilder.

Basert på disse referansene ligger leienivået på ca. kr. 1 250 – 2 150,- per m² P-rom.

Leiligheter

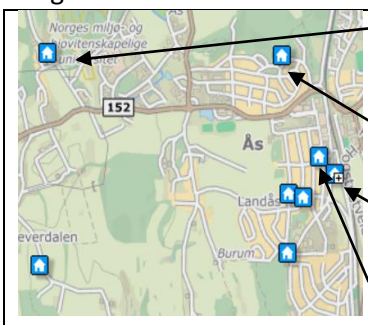	Det leies ut en sokkeleilighet i Klokkerveien 7 på campus Ås for kr. 8 500,- per mnd. Leiligheten har 0 soverom og et P-rom på 60 m². Bruttoarealet er 68 m². leiligheten har eldre standard basert på bilder.
	I Lyngveien 16B leies det ut en 3-roms leilighet for kr. 13 000,- per mnd. Leiligheten har et P-rom på 68 m². Leiligheten har eldre standard basert på bilder.
	I Raveien 6B leies det ut en 3-roms leilighet for kr. 15 000,- per mnd. Leiligheten har et P-rom på 57 m² og et bruttoareal på 66 m². Leiligheten er fra 2017 og har moderne standard
	I Moerveien 13B leies det ut en 2(3) -roms leilighet i et hus for kr. 13 500,- per mnd. Leiligheten har et P-rom på 46 m². Huset fremstår nyoppusset på bilder.
De fire andre leilighetene lå mellom kr 8 000-15 000,- per mnd., hvorav to leiligheter med ett soverom lå ute for 8 000 og 10 000,- per mnd. En leilighet med 2 soverom lå ute for 13 000,- per mnd og en med 43 soverom lå ute for 15 000,- per mnd.	

Basert på disse referansene ligger leienivået på ca. kr. 1 500 – 3 150,- per m^2 P-rom. I øvre sjikt er en ny leilighet fra 2017.

Definisjon av markedsleie
Markedsleie er etter OPAKs syn hva markedet er villig til å betale ved en standard leiekontrakt og med eiendommen ledig. Markedsleie er ikke det maksimale en enkelt potensiell leietaker er villig til å betale for et enkelt lokale, men den leien som av flere uavhengige interessenter anses som passende. En enkelt leietaker kan av spesielle årsaker være villig til å betale spesielt høy leie for å sikre seg en eiendom, men dette er ikke markedsleie. Markedsleie baserer seg på en ordinær leiekontrakt som kan indeksreguleres hvert år.

Eiendommen er vurdert ledig i markedet og basert på markedsleie. Videre legges til grunn at alle måleverdige arealer, som definert i Norsk Standard NS 3940, inkluderes i leiearealene, også teknisk rom og annet som er nødvendig for eiendommens drift. Alle arealer som leies ut måles i bruttoareal BTA.

Vurderte leienivåer
Kontorleie
Basert på markedsrapportene fremgår det at kontorleie sør for Oslo ligger rundt 1 200,- per m^2 BTA/år for moderat/generelt høy standard. Ås er beliggende et stykke utenfor Oslo, hvor leienivåene generelt er lavere. I Metra Næringsmelding sitt siste kundemagasin oppgis leier for lokaler i Moss og Vestby, hvor det fremgår at kontordelen i kombinasjonsbygg leies ut for rundt kr. 950,- per m^2 BTA/år.

Basert på dette vurderer vi at kontorlokaler normalt vil ligge i et spenn mellom kr. 850-1 200,- per m^2 BTA/år.

Den vurderte eiendommen har en del undervisnings-, forsknings- og lablokaler som det ikke finnes tilgjengelig markedsdata på. Vi har derfor valgt å se slike lokaler i sammenheng med kontor.

Lagerleie
Basert på markedsrapportene fremgår det at lagerleie i Vestby normalt ligger på mellom kr. 500-700,- per m^2 BTA/år og toppleie på kr. 800,- per m^2 BTA/år. Ås er beliggende nært Vestby, men vurderes å ha mindre lageretablering. I Metra Næringsmegling sitt siste kundemagasin oppgis leier for lokaler i Moss, hvor det fremgår at lagerdelen i kombinasjonsbygg leies ut for rundt kr. 750,- per m^2 BTA/år.

Basert på dette vurderer vi at lagerlokaler normalt vil ligge i et spenn mellom kr. 400 - 700,- per m^2 BTA/år.

På den vurderte eiendommen er det en del veksthus og driftsbygninger for landbruksmaskiner og husdyr. Vi har valgt å se slike lokaler i sammenheng med lager og dels kontor. I noen tilfeller er det bygg som har såpass lav standard at de faller utenfor det oppgitte spennet. Tilsvarende har vi sett nyere driftsbygninger som vurderes høyere enn spennet. Det finnes også noen mer spesielle bygg som ikke kan leies ut alene eller har spesielt særegen bruk som vi har vurdert uavhengig av spennet.

Boligleie
Basert på finn.no leies det ut eneboliger og leiligheter på og rundt campus. Disse leies ut for mellom 8 000 – 21 000,- per mnd., avhengig av beliggenhet, standard og antall rom. Vi har ikke befart boligbyggene på campus innvending og er ikke kjent med antall utleiebare rom. Vi har derfor basert oss på oppgitt areal og sett det i sammenheng med referansene på hus rundt 150 m^2 BTA og sett hva som er typisk antall soverom. Leienivå på bolighusene lå rundt 1 250 – 2 150,- per m^2 P-rom. Bolighusene vi har vurdert er oppgitt i BTA. Vi har skjønnsmessig lagt til grunn kr. 900 - 1 100,- per m^2 BTA.

Oppsummert
De vurderte byggene består i mange tilfeller av flere formål. Vi har valgt å gruppere eiendommen på følgende måte:

- Kontor, undervisning, forskning: kr. 800 - 1 200,- per m^2 BTA/år
- Lager, veksthus, driftsbygninger, uthus: kr. 400 - 800,- per m^2 BTA/år
- Bolig: kr. 900 - 1 100,- per m^2 BTA/år.

Vi har beregnet markedsverdien til bebyggelsen i vedlagt Excel-skjema

Område	Areal	Årlig markedsleie	Gjennomsnitt markedsleie
Sentral campus	64 569	68 570 509	1 062
Campus Syd	6 008	4 763 441	793
Campus Øst	24 645	21 749 446	882
Campus Vest	11 779	9 313 214	791
Campus Nord	14 046	7 638 067	544
Ås Gård	13 709	12 469 189	910
Årungen	90	27 090	300
Sommerfjøset	227	158 900	700
Vollebekk	4 860	3 532 640	727
Norderås	3 469	2 863 318	825
Frydenhaug	382	352 400	923
Slørstad	2 092	209 200	100
Sum	**145 876**	**131 647 415**	**902**

Avkastningsverdi

Brutto årlig leie
Det er lagt til grunn følgende årlig leie: 131 647 415

Arealledighet
Arealledigheten i bysentrale områder er vanligvis 4 – 7 % og 7-9 % i mer perifere strøk.
Ledigheten/leiesvikten for den vurderte eiendommen er skjønnsmessig vurdert til:
Arealledighet, % : 10
Kommentar : Ifølge Akershus Eiendom er kontoledigheten i Oslo Outer South på under 7,5%.

Eierkostnader

En ordinær leiekontrakt forutsetter at gårdeier bl.a. dekker kostnader til administrasjon, forsikring, eventuelt eiendomsskatt, utvendig vedlikehold og periodisk vedlikehold og utskiftninger av større tekniske anlegg, normalt mellom kr 150,- og kr 350,- pr.m² BTA/år for kontorbygg, og kr 80,- til kr 100,- pr m² BTA/år for lagerbygg/kombibygg.

Innenfor eget areal dekker leietaker egne kostnader til energi, rengjøring, renovasjon, service og løpende innvendig vedlikehold ved en vanlig standard leiekontrakt. Kort gjenværende leietid kan medføre behov for høyere eierkostnader pga. behov for oppgraderinger for lokaler som snart blir ledige, og som ikke allerede er oppgradert av fraflyttende leietaker. Et høyt antall leiekontrakter påvirker også eierkostnadene oppover.

For denne eiendommen er årlige eierkostnader vurdert til:

Årlige eierkostnader, kr/m² BTA : 175

Kommentar : Ifølge Basalerapporten 2018 ligger eierkostnadene til deres utvalg mellom kr. 137-361,- per m^2 BTA/år. Gjennomsnittet i deres utvalg er kr. 238,- per m^2 BTA/år. Det er basert på 74 eiendommer med snittareal på 7 660,- per m^2 BTA og snittleie på 1 915,- per m^2 BTA/år. 34% av eiendommen er i Oslo. De resterende byggene ligger spredt over hele landet.

Netto årlig leie

Netto årlig leie er vurdert til, basert på markedsleie for ledige lokaler:

	Brutto årlig leie				kr.	131 647 415
÷	Antatt arealledighet / leiesvikt i %	10			kr.	13 164 742
=	Redusert brutto leie				kr.	118 482 674
÷	Antatte eierkostnader kr./m²/år:	175	m²:	145 876	kr.	25 528 300
=	**Netto årlig leie**				**kr.**	**92 954 374**

Kapitaliseringsrente

Basis for vurdering av kapitaliseringsrente er først og fremst sammenligning med den alternative avkastning en investor kan få ved investering i sikre og risikofrie 10 års statsobligasjoner. Dernest legges til en risikopremie for den spesifikke eiendomsinvestering som følge av at det kan være mer risikofylt å investere i eiendom enn i statsobligasjoner. Dersom f.eks. avkastning av 10 års statsobligasjoner er 5,5 % og inflasjonen er 2,5 %, er realrenten differansen 3,0 %.

Det vurderes i tillegg til realrenten et risikotillegg som følge av antatt utvikling i realrentenivå, risiko ved fremtidige leieinntekter og utleie av den spesifikke eiendom, leietakers soliditet, eiendommens beliggenhet, bruk, tilstand, alder og attraktivitet i markedet. Det er derfor av vesentlig betydning for vurdering av kapitaliseringsrente om en eiendom har en perifer beliggenhet med kort leiekontrakt eller er ledig, eller om den har en sentral beliggenhet og i tillegg har en kommunal eller statlig leietaker med lang leiekontrakt og sikre leieinntekter.

Normalt vurderes kapitaliseringsrenten til mellom 4 % og 7 % for f.eks. kontorbygg i bysentrale områder og mellom 7 % og mer i mer perifere områder.

Men dette endres fort ved markedssvingninger.

Ut fra en samlet vurdering har vi for denne eiendommen benyttet følgende kapitaliseringsrente:
Kapitaliseringsrente , % : 7,50
Kommentar : Ifølge Union Gruppen er prime yield i ytre syd 5,10%.

Avkastningsverdi

Avkastningsverdien er en av flere faktorer som er med på å fastsette markedsverdien for eiendommen slik den fremsto som et selvstendig omsetningsobjekt. Ved vurderingen er det tatt hensyn til eiendommens beliggenhet og tomt, bygningens tekniske og vedlikeholdsmessig stand, samt bygningens effektivitet.

Ved vurderingen er det også tatt hensyn til dagens leieinntekt, leiekontraktens reguleringsmuligheter og varighet på leiekontraktene, sett i relasjon til dagens markedsleie. Driftskostnader er også vurdert.
Basert på ovenstående er kapitalisert verdi av netto leieinntekter vurdert til:

kr.	92 954 374	x	100	:	7,50	=	kr	1 239 391 653

Sum avrundes til kr. 1 239 000 000

Følsomhetsanalyse ved alternative avkastningskrav

Nedenfor er vist hvorledes avkastningsverdien endres som følge av andre kapitaliseringsrenter:

Nettoleie i kr	Avkastningskrav %	Verdi kr
92 954 374	8,25	1 126 719 685
92 954 374	8,00	1 161 929 675
92 954 374	7,75	1 199 411 277
92 954 374	**7,50**	**1 239 391 653**
92 954 374	7,25	1 282 129 297
92 954 374	7,00	1 327 919 629
92 954 374	6,75	1 377 101 837

Referanser

Som kontroll har vi undersøkt referanser

Salgsobjekter Metra Næringsmegling

I Metra Næringsmeglings siste kundemagasin selges et utleid næringsbygg med 240 m^2 BTA kontor og 375 m^2 BTA lager i Evjeløkka 7 på Rolvsøy for kr. 6,5 mill. Det tilsvarer kr. 10 570,- per m^2 BTA.

I Sarpsborgveien 2 i Råde selges butikklokaler på 980 m^2 BTA for kr. 8 mill. Det tilsvarer kr. 8 163,- per m^2 BTA. 90% av eiendommen er leid ut.

I Øysteins gate 1 i Moss selges et bygg som annonseres som utviklingsprosjekt med rammetillatelse til 5 leiligheter. Bygget er på 500 m^2 BTA og selges for 6 mill. Det tilsvarer kr. 12 000,- per m^2 BTA. Tomten er på 526 m^2 tomt. Prisantydningen tilsvarer 11 406,- per m^2 tomt.

Salgsobjekter Eiendomsmegler 1 Næringsmegling Østfold Akershus
Eiendomsmegler 1 selger 08.10.2019 en utleid eiendom i Høgdaveien 4 i Vestby på 2 200 m^2 for 20 mill. 9 090,- per m^2 BTA. Bygget er fra 1966 og benyttes til butikk/handel. Eiendommen fremstår i enkel standard.

Salg av skolebygg
Ifølge Vestfold fylkeskommune sine hjemmesider (2019) ble Skippergata 6 som huser deler av Horten videregående skole solgt til private for kr. 60 mill. Ifølge Nordeca Insight har bygget et fotavtrykk på ca. 2 500 m^2 BYA og er på 4 etasjer. Det tilsvarer ca. 10 000 m^2 BTA. Salgsverdien er dermed ca. 6 000,- per m^2 BTA.

Ifølge Estate Nyheter(2018) ble Kongsgård Allé 20 i Kristiansand som huser Kristiansand International School solgt for kr. 415,5 mill. Kjøper var et britisk investeringsselskap. Skole endommen er bebygd med 15 800 m^2 BTA, som tilsvarer kr 26 297,- per m^2 BTA. Eiendommen er fullt utleid til Kristiansand kommune og har gjenværende leietid på 20 år. Leieinntektene er på 19,2 millioner, som tilsvarer kr. 1 215,- per m^2 BTA/år.

I 2017 la Lenvik kommune ut Finnsnes ungdomsskole for salg. Ifølge Estate Nyheter (2019) er eiendommen ennå ikke solgt. Prisantydning er kr. 49,5 mill. for 6 000 m^2. Det tilsvarer kr. 8 250,- per m^2 BTA. Skolen beskrives som en slitt skole fra 1960 på over ni mål tomt. Eiendommen er regulert til bolig og tjenesteyting og inneholder undervisningsrom, administrasjon/kontor, badebasseng og gymsal.

Ifølge Ørland kommune sine nettsider (2019) signerte Forsvarsbygg og Ørland kommune avtale om kjøp av Hårberg skole for 100 mill i 2016. Forsvarsbygg kjøper skolen. Det fremgår av NRK (2015) at staten kjøper Hårberg skole, som ligger innenfor støysonen til den nye kampflybasen. Ifølge Nordeca Insight er bebyggelsen ca. 4 000 m^2 BTA. Det tilsvarer kr. 25 000,- per m^2 BTA. I artikkelen i NRK fremgår det at en helt ny skole vil koste mellom 100-130 millioner. Antakelig er dette lagt til grunn i transaksjonen. ¨

Salg av sykehus
Ifølge Fredrikstadblad (2014) ble Fredrikstad Sykehus solgt for 130 millioner. Prisantydningen var først satt til 255 millioner kroner, salgsprisen er nesten halv pris. Sykehusbygningene ble oppført i 1956 og oppgis å være 55 000 m^2 BTA. Det tilsvarer kr. 2 363,- per m^2 BTA. Tomten er oppgitt til 34,9 daa. Det tilsvarer kr. 3 725,- per m^2 tomt. På salgstidspunktet hadde det vært lansert mange planer for området, blant annet er det foreslått å bruke området til videregående skole og boliger. I Fredrikstadblad (2015) fremgår det at det planlegges 1 000 nye leiligheter på tomten.

Ifølge NRK (2015) ble Kragerø sykehus kjøpt av kommunen til takst på 63 millioner kroner. Ifølge Varden (2015, oppdatert 2019) er sykehuset 7 828 m^2 BTA og 17 daa tomt. Det tilsvarer kr. 8 048 per m^2 BTA og kr. 3 705,- per m^2 tomt

Ifølge Drammens Tidene (2015) ble Lier sykehus solgt for 80 millioner. Ifølge Estate Nyheter (2015, oppdatert 2017) ble hele tomten til Lier sykehus lagt ut for salg i fire parseller. «*De fire parsellene består av et utviklingsområde, der tomtearealet etter fradeling er planlagt til ca. 68 mål. Bygningsmassen utgjør brutto anslagsvis ca. 21 450 kvadratmeter og er «svært variert». Flere av byggene har altså stått avstengt i mange år og har «store og omfattende bygningsmessige rehabiliteringsbehov».* Det tilsvarer kr. 3 729 per m^2 BTA og kr. 1 176,- per m^2 tomt

Verdikonklusjon

Salgsverdi er den pris man kan påregne at flere uavhengige interessenter til eiendommen vil være villig til å betale for den på dato for vurderingen. En enkel interessent kan av spesielle årsaker være villig til å betale en spesielt høy pris for å sikre seg eiendommen. Dette er ikke salgsverdi. Ved vurderingen er det tatt hensyn til eiendommens beliggenhet og tomtens attraktivitet.

Iht. mandat fra oppdragsgiver er eiendommen vurdert i to alternativ med følgende forutsetninger;

1. Verdien skal fastsettes på bakgrunn av eiendommens gjenanskaffelsesverdi, dvs. **teknisk verdi.**
2. Eiendommens markedsverdi, ved salg **uten statlig leiekontrakt** med tilsvarende bruk som i dag, men på **markedsmessige betingelser**. Eiendommen takseres iht. påregnelig utnyttelse (gjeldende regulering og kommuneplan).

Eiendommens verdi, slik den befant seg ved befaringen og ledig for kjøper er vurdert til:

1) Teknisk verdi

Teknisk verdi bygg

Teknisk verdi bygg, kr	Eksisterende bygg, m² BTA	Verdi, kr/m² gulvareal BTA
1 669 973 199	145 876	11 448

Teknisk verdi tomt eks. potensiale og LNFR

Teknisk verdi tomt, kr	Eksisterende bygg, m² BTA	Verdi, kr/m² gulvareal BTA
338 597 304	145 876	2 321

Teknisk verdi bygg + tomt

Teknisk verdi bygg + tomt, kr	Eksisterende bygg, m² BTA	Verdi, kr/m² gulvareal BTA
2 008 570 503	145 876	13 769

Tillegg for utbyggingspotensiale, LNFR og festeforhold

Utbyggingspotensiale	kr	639 000 000
LNFR	kr	22 000 000
Kapitalisert verdi av festeinntekt	kr	19 000 000
Sum	**kr**	**680 000 000**

2) Markedsverdi

Eiendommens salgsverdi, slik den befant seg ved befaringen og ledig for kjøper er vurdert til:

Kapitalisert verdi av netto leieinntekter	kr	1 239 000 000
Utbyggingspotensiale	kr	639 000 000
LNFR	kr	22 000 000
Kapitalisert verdi av festeinntekt	kr	19 000 000
Salgsverdi	**kr**	**1 919 000 000**

SALGSVERDI KR 1 919 000 000

Salgsverdi bygg, kr	Eksisterende bygg, m² BTA	Verdi, kr/m² gulvareal BTA
1 239 000 000	145 876	8 494

Oslo, 28.01.2020

For OPAK

Øystein Dieseth
Avdelingsleder/takstmann

Thomas Rochstad-Johannesen
Takstmann/Eiendomsrådgiver

Christian Kleivene
Eiendomsrådgiver

☑	Egenkontroll		☑ Sidemannskontroll	☐	Overordnet kontroll
	28.01.2020	TRJ	29.11.2019 ØD		Dato Initialer

Distribuert til:
Norges miljø- og biovitenskapelige universitet v/ Kjersti Sørlie Rimer
Kopi til Statsbygg v/Marita Aastad Pedersen